1. INTRODUCCION

El sistema de archivos es la estructura en la que se almacena la información de manera ordenada, facilitando la escritura, lectura y búsqueda de archivos, garantizando que el usuario pueda identificarlos de manera ágil.

2. OBJETIVO

Establecer los lineamientos técnicos para el renombramiento, almacenamiento y alistamiento de la información.

3. ALCANCE

Gestionar la información de una forma eficiente enfocada a la formación y actualización catastral de los proyectos en curso acordes a las fuentes de financiación ya sean propias o tercerizadas.

4. DEFINICIONES

PDF: Del inglés "*Portable Document Format*" formato de documento portable compuesto por imágenes vectoriales o acompañado de texto.

ZIP: Formato de compresión de archivos digitales sin pérdida de calidad, reduciendo su tamaño facilitando el transporte la información.

Divipola: Codificación adoptada por el Departamento Administrativo Nacional de Estadística "DANE" la cual permite consultar departamentos, municipios, distritos y centros poblados en forma numérica la "División Político - Administrativa de Colombia".

Diccionario de Nombres: Documento el cual presenta las abreviaciones de las palabras más utilizadas dentro del sistema de archivos.

Estructura de carpetas: Árbol de directorios con una carpeta inicial llamada raíz, la cual se complementa por subdirectorios en formato de cascada generando una jerarquía de los datos.

Capa Vectorial: Archivo en formato "*Shape*" compuesto por varios archivos auxiliares nativo u originario de ESRI que representan formas, también se pueden encontrar en otros formatos como lo son DWG, GML, XML, GPX Geopackage, KML MVT entre otros.

Ortofotografía: Representación del terreno mediante una fotografía corregida y libre de error, la cual está asociada a una escala definida, sin deformaciones o geoformas.

Bases de Datos: Conjuntos de datos geográficos que almacenan información ya sea vectorial o raster, estos datos se caracterizan por tener una posición, forma geométrica, dimensión y atributos descriptivos.

ECW: Formato de compresión de imágenes "Enhaced Compresion Wavelet" utilizado para reducir el peso de los formatos ráster sin perder resolución espacial y calidad.

TIF: Formato de imagen de alta calidad (Tagged Image File Format) utilizado comúnmente para almacenar imágenes ráster. Este formato es especialmente adecuado para la representación de datos geoespaciales debido a su capacidad para manejar grandes volúmenes de información.

CSV: Formato de archivo de texto que utiliza comas para separar valores, comúnmente utilizado para la representación de datos tabulares. Facilita la importación y exportación de datos entre diferentes sistemas.

5. DESARROLLO

Con el fin de poder realizar actividades de validación de calidad de los productos catastrales derivados de los procesos de formación y actualización catastral, en este instructivo se han planteado lineamientos específicos para la entrega de dichos productos. A continuación, se definen los lineamientos para la estructura de carpetas y el nombrado de archivos de la información catastral.

5.1.1. LINEAMIENTOS ENTREGA DE PRODUCTOS CATASTRALES

Este lineamiento aplica para operadores contratados por el IGAC u otras entidades, en el marco de los procesos de formación y actualización catastral que se adelantan en la zona urbana y rural de distintos municipios del país donde el Instituto Geográfico Agustín Codazzi (IGAC) presta el servicio catastral por excepción.

- **ESPECIFICACIONES PARA CADA NIVEL Y SUBNIVEL DE INFORMACIÓN**

Con el fin de establecer una estructura de capetas para la entrega de la información derivada de los procesos catastrales de formación o actualización, se presentan a continuación los niveles de información establecidos:

- **Nivel I:** Corresponde al Departamento donde se está desarrollando el proceso de levantamiento catastral. Se deberá crear una carpeta nombrada de acuerdo con la codificación político-administrativa del DANE para departamento, que corresponde a un código de dos posiciones.
  Ejemplo: El código para el departamento de Cundinamarca es 25.

NIVEL I
25

Diagrama 1. Ejemplo Nivel I

- **Nivel II.** Corresponde al Municipio donde se está desarrollando el proceso de levantamiento catastral. Se deberá crear una subcarpeta dentro de la carpeta de departamento nombrada de acuerdo con la codificación político-administrativa del DANE para municipio, que corresponde a un código de tres posiciones.
  Ejemplo: El código para el municipio de Chía es 175.

NIVEL I	NIVEL II
25	175

Diagrama 2. Ejemplo Nivel II

- **Nivel III.** Corresponde a la fuente de financiación sean propias o tercerizadas para el municipio donde se está desarrollando el proceso de levantamiento catastral. Se deberá crear una subcarpeta dentro de la carpeta de municipio la cual tendrá el nombre de la fuente de financiación como "IGAC", "ANT", "PGN", "FAO", "FCP", "SGR", "BID" o "ART".

NIVEL I	NIVEL II	NIVEL III
25	175	igac

Diagrama 3. Ejemplo Nivel III

- **Nivel IV.** Está relacionado a la etapa en la que se encuentra el desarrollo del proceso de levantamiento catastral. Encontrando cuatro (4) etapas que son: "01_Preoperativos", "02_Operativos", "03_Postoperativos" y "04_Transversal".
  - **Etapa Preoperativa:** Esta fase se centra en la planificación y organización necesaria antes de comenzar el trabajo en campo, esperando un plan detallado que garantice eficacia de la intervención.
  - **Etapa Operativa:** Se lleva a cabo el levantamiento de datos de manera efectiva, es decir, la recolección y validación de datos catastrales en terreno.
  - **Etapa Postoperativa:** Se verifica, analiza y se da seguimiento a los resultados obtenidos, así como procesos relacionados con la gestión de los datos.
  - **Etapa Transversal:** Actividades aplicables en todas las etapas.

NIVEL I	NIVEL II	NIVEL III	NIVEL IV			
25	175	igac	01_preo	02_opera	03_post	04_transv

Diagrama 4. Ejemplo Nivel IV

En cada etapa encontrada, hay subdirectorios en los que se almacena información del proceso de levantamiento catastral.

Para la <u>Etapa Preoperativa</u> se tiene:

- **01_Propuesta:** Documentación técnica y administrativa correspondiente a la propuesta inicial para el desarrollo del proyecto, con análisis de alcance, objetivos, metodología, cronograma preliminar, identificación de recursos necesarios (técnicos, financieros) y una evaluación inicial de las áreas a intervenir.

Diagrama 5. Ejemplo subdirectorio Propuesta

- **01_Documento (Propuesta):** Presenta de manera estructurada los planes, estrategias y metodología a seguir, definiendo objetivos generales y específicos, cronograma de actividades, análisis de riesgos y acciones de mitigación propuestas, de tal forma que se comprenda la visión integral y metas del proyecto.

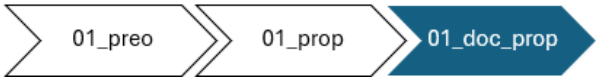

Diagrama 6. Ejemplo subdirectorio Documento Propuesta

- **02_Terminos_de_Referencia:** Establece de manera formal y técnica las especificaciones para la ejecución de los servicios y actividades que forman parte del proyecto, incluyendo las obligaciones de las partes, los entregables requeridos y los plazos estipulados, sirviendo como guía para garantizar el cumplimiento de los objetivos del proyecto alineado con la normatividad vigente.

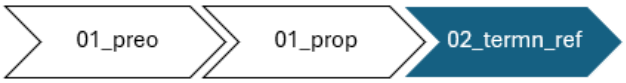

Diagrama 7. Ejemplo subdirectorio Términos de Referencia

- **02_Carta_Aceptación:** Acuerdo entre las partes involucradas en el proyecto, específicamente entre la entidad ejecutora y la autoridad competente. En esta carta se establecen los compromisos mutuos, responsabilidades asumidas por cada parte y las condiciones bajo las cuales se desarrollará el proyecto. Se especifica la aceptación de los términos establecidos en la propuesta inicial, en donde se garantice la alineación con los objetivos y las disposiciones para dar inicio oficial al proceso.

Diagrama 8. Ejemplo subdirectorio Carta de Aceptación

- **03_Contrato_y_Modificaciones:** Respaldan los acuerdos legales y administrativos establecidos para que se ejecute el proyecto, con contratos firmados entre la entidad ejecutora y las partes contratantes, detallando términos, condiciones, alcances y responsabilidades de cada uno. Adicional a ello, se registran las modificaciones o adendas realizadas a dichos contratos durante la fase de ejecución, como ajustes en el alcance, cronograma o presupuesto.

Diagrama 9. Ejemplo subdirectorio Contrato y Modificaciones

- **04_acta_ini:** Este documento formaliza que todas las condiciones necesarias para iniciar el proceso operativo han sido verificadas y aprobadas por todos los actores. En el acta se constata que se han cumplido los requisitos previos establecidos, con validación de los recursos, revisión de términos de referencia y la conformidad con los acuerdos contractuales. Adicional a ello, se fijan plazos de seguimiento, con el fin de que el proyecto inicie con todos los aspectos técnicos, legales y operativos.

Diagrama 10. Ejemplo subdirectorio Acta de Inicio

- **05_Plan_Gestión_Proyectos:** Planes necesarios para la gestión y planificación general del proyecto, con aspectos técnicos, logísticos, ambientales y sociales que deben ser considerados para la posterior ejecución. El plan establece estrategias precisas para la gestión de recursos, tiempo, y costos, junto con procedimientos de supervisión, asegurando el control de calidad y gestión de riesgos con el fin de promover un desarrollo eficiente y sostenible.

Diagrama 10. Ejemplo subdirectorio Plan Gestión de Proyectos

  - **01_Plan_Operativo:** Detalla actividades específicas a ejecutar, con un enfoque práctico y orientado a la implementación logística, que permita coordinar el trabajo en campo, asignación de tareas al personal involucrado y el despliegue de recursos técnicos en las áreas de intervención. También coordina con autoridades locales y las demás partes interesadas para garantizar el cumplimiento de los plazos y el desarrollo de supervisión y control de calidad sobre la recolección, verificación y procesamiento de datos.

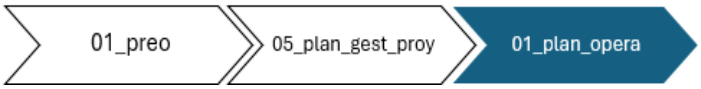

Diagrama 11. Ejemplo subdirectorio Plan Operativo

  - **02_Plan_Gestión_Integral:** Estrategias para abordar de manera coordinada todos los aspectos relevantes, considerando los ámbitos administrativos, técnicos, financieros y sociales, detallando recursos, seguimiento de presupuesto, planificación de las actividades técnicas y la resolución de los aspectos normativos. Adicional a esto, las dimensiones sociales y ambientales serán integradas, de esta forma se asegura la participación activa de la comunidad.

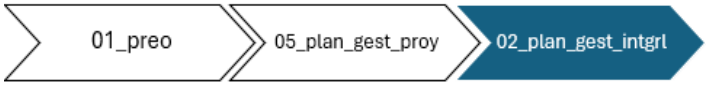

Diagrama 12. Ejemplo subdirectorio Plan Gestión Integral

  - **03_Plan_Calidad:** Procedimientos establecidos para garantizar calidad en la verificación de los datos recolectados, buscando precisión conforme a los estándares técnicos requeridos. Se describen los mecanismos de control de calidad tanto en el trabajo en campo como en los procesos de análisis para asegurar que los resultados finales sean confiables acorde a los requisitos del proyecto.

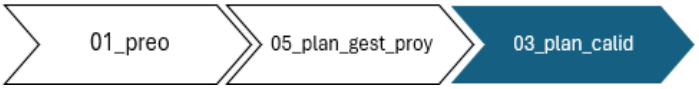

Diagrama 13. Ejemplo subdirectorio Plan Calidad

  - **04_Plan_Gestión_Ambiental:** Identificación, gestión y mitigación de los impactos ambientales y sociales, definiendo estrategias que garanticen que el proyecto cumpla con las normativas ambientales locales, nacionales y estándares de sostenibilidad con

medidas preventivas y correctivas para protección de la biodiversidad, ecosistemas, manejo adecuado de residuos y la conservación de los recursos naturales.

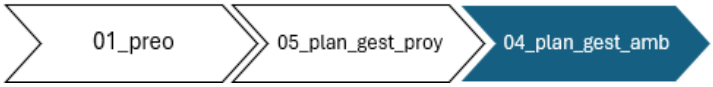

Diagrama 14. Ejemplo subdirectorio Plan Gestión Ambiental

- **01_PGAS_(Plan de Gestión Ambiental y Social):** Presenta un plan detallado que combina las consideraciones ambientales y sociales, con estrategias para la gestión sostenible de los recursos naturales, pero abordando la identificación de los grupos sociales presentes en las áreas de intervención y medidas necesarias para asegurar actividades de desarrollo inclusivo con las comunidades locales.

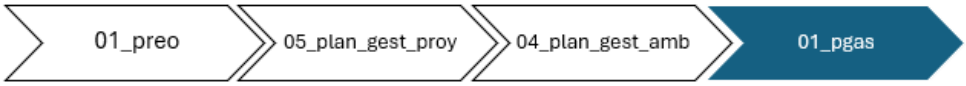

Diagrama 15. Ejemplo subdirectorio PGAS

- **02_MGAS_(Marco de Gestión Ambiental y Social):** Establece el marco normativo y estratégico que guiará la implementación del PGAS (Plan de Gestión Ambiental y Social). Define políticas generales, regulaciones y directrices que deben asegurar el cumplimiento de los estándares ambientales y sociales. Así mismo, se establece los mecanismos de supervisión y evaluación que aseguraran que las medidas ambientales y sociales propuestas sean adecuadamente implementadas, permitiendo hacer ajustes necesarios entre los objetivos técnicos y los impactos en la comunidad.

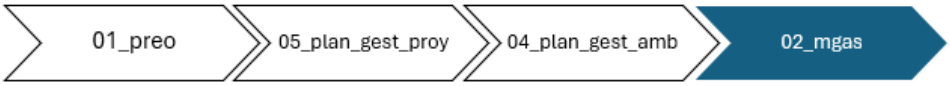

Diagrama 16. Ejemplo subdirectorio MGAS

- **06_Pre_Reconocimiento:** Información preliminar y evaluación de las condiciones del terreno y las áreas a intervenir, con un análisis de la zona, identificación de puntos críticos y recopilación de datos geográficos, antes de dar inicio al proceso catastral.

Diagrama 17. Ejemplo subdirectorio Pre-reconocimiento

  - **01_Diagnóstico:** Estado actual del territorio; se recopilan datos sobre las condiciones geográficas, sociales, económicas y ambientales del área, con ayuda de estudios topográficos, cartográficos, uso del suelo, así como la identificación de infraestructura existente, y distribución poblacional.

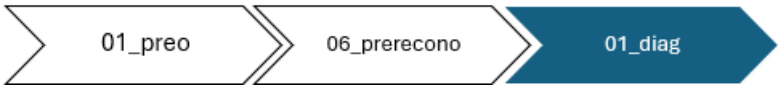

Diagrama 18. Ejemplo subdirectorio Diagnostico

    - **01_Preliminar (Básico / Caracterización):** Diagnostico preliminar del área objeto del proceso, abordando aspectos de infraestructura existente, condiciones socioeconómicas de la población y uso del suelo. Proporciona un análisis inicial

del contexto en el cual se va a llevar a cabo el levantamiento catastral, y como se recoge información sobre accesibilidad y los recursos naturales de la zona.

Diagrama 19. Ejemplo subdirectorio Preliminar (Básico – Caracterización)

- **02_Catastral:** Informes relacionados con la situación catastral previa del municipio en cuestión, proporcionando el estado actual del catastro. Contiene información sobre las bases catastrales existentes, delimitaciones previas de predios y propiedades, así como los registros y documentos oficiales de la gestión catastral y posibles discrepancias entre el catastro oficial y los estudios realizados en campo, con el fin de actualizar y corregir las bases catastrales y garantizar precisión en el levantamiento de la información.

Diagrama 20. Ejemplo subdirectorio Catastral

- **01_Marcas:** Identificación, validación y documentación de los puntos de referencia físicos establecidos en el terreno, con informes de campo sobre las marcas geodésicas, hitos topográficos y demás puntos usados para la delimitación de propiedades y representación cartográfica, registrando las coordenadas geográficas, el método de medición empleado en función de la precisión obtenida durante el proceso.

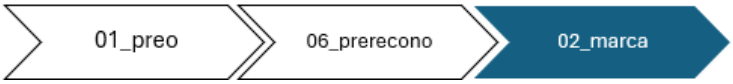

Diagrama 21. Ejemplo subdirectorio Marcas

- **01_Consolidación:** Recopila los registros sobre la ubicación, estado y características de las marcas geodésicas y demás puntos de referencia existentes en el terreno. Se documenta las condiciones actuales de las marcas, como su visibilidad, acceso y estabilidad, para que la recolección de datos sea fiable y facilite la continuidad del levantamiento de información.

Diagrama 22. Ejemplo subdirectorio Consolidación

- **01_urbano:** Documentos, mapas y registros relacionados con las marcas urbanas, detallando los puntos de referencia establecidos dentro del entorno urbano, como hitos, mojones y otros elementos geodésicos, además de los planos y mapas que visualizan su ubicación en el terreno.

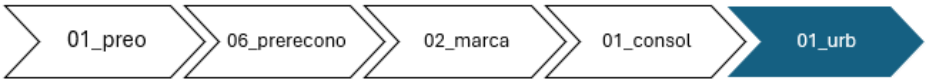

Diagrama 23. Ejemplo subdirectorio Urbano

- **01_rural:** Documentos, mapas y registros relacionados con las marcas rurales, detallando los puntos de referencia establecidos dentro del

territorio rural, como hitos, mojones y otros elementos geodésicos, además de los planos y mapas que visualizan su ubicación en el terreno.

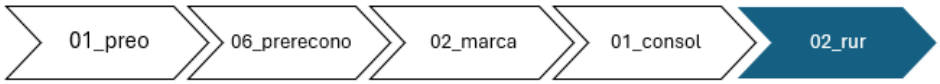

Diagrama 23. Ejemplo subdirectorio Rural

- **03_Fuente_Espacial:** Fuentes de datos geoespaciales que se van a usar, como imágenes satelitales, datos de sistemas de información geográfica (SIG), cartografía digital, ortofotos, etc., con la resolución, precisión y la fecha de adquisición de los datos espaciales, garantizando su calidad para el análisis y georreferenciación de la información.

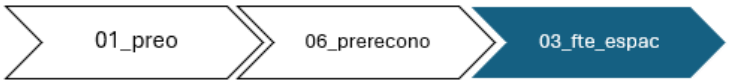

Diagrama 24. Ejemplo subdirectorio Fuente Espacial

  - **01_GDB:** Organiza la información georreferenciada, la cual contiene capas de datos espaciales que incluyen, pero no se limitan a, información sobre límites de predios, infraestructuras, redes viales, hidrografía y variables relevantes para el análisis espacial. la cual contiene información georreferenciada que servirá para los respectivos análisis espaciales.

Diagrama 25. Ejemplo subdirectorio GDB

  - **02_MPK:** Paquetes de mapas que incluyen los mapas digitales, estos almacenan una serie de capas temáticas con la delimitación de predios, infraestructura, redes viales, y elementos geográficos, organizados en un formato que facilita su acceso y análisis dentro del sistema de información geográfica (SIG). Estos paquetes de mapas permiten visualizar la información geoespacial de manera eficiente y precisa, con el fin de facilitar la toma de decisiones durante la recolección de datos y la validación en terreno.

Diagrama 26. Ejemplo subdirectorio MPK

    - **01_urbano:** Paquetes de mapas urbanos, que contienen información geoespacial específica sobre las zonas urbanas a catastrar, incluyendo mapas que representan la infraestructura urbana, delimitación de predios, redes viales, servicios públicos, zonas verdes, edificaciones y elementos relevantes del entorno urbano, con metadatos que detallan la fuente, la escala, la resolución y la fecha de obtención de los datos.

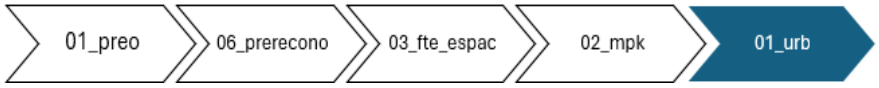

Diagrama 27. Ejemplo subdirectorio Urbano

- **01_rural:** Paquetes de mapas rurales, que contienen información geoespacial específica sobre las zonas rurales a catastrar, incluyendo mapas que representan la distribución de predios rurales, límites territoriales, redes viales, cuerpos de agua, usos del suelo, y elementos relevantes del entorno rural, con metadatos que detallan la fuente, la escala, la resolución y la fecha de obtención de los datos.

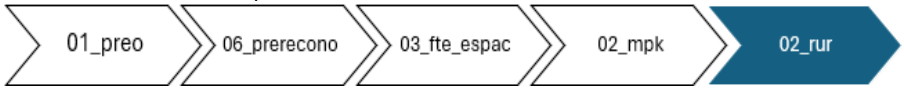

Diagrama 28. Ejemplo subdirectorio Rural

- **01_Dashboard:** Herramientas y plataformas de visualización que permiten el análisis interactivo de los datos recolectados, integrando diversas fuentes de información geoespacial, estadística y operativa, facilitando la visualización en tiempo real del avance del proyecto. A través de interfases gráficas, los usuarios pueden realizar consultas, generar mapas temáticos, analizar y tomar decisiones basadas en los datos recolectados en campo.

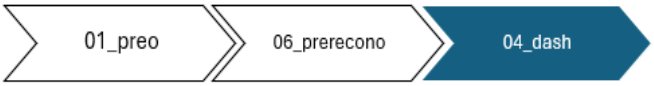

Diagrama 29. Ejemplo subdirectorio Dashboard

- **01_Dash:** Archivos y configuraciones relacionados con el dashboard de monitoreo utilizado para el seguimiento del levantamiento catastral. El dashboard proporciona una interfaz centralizada para el análisis y control de los datos del proceso, permitiendo visualizar en tiempo real el progreso de las actividades, la calidad de la información recolectada y el cumplimiento de los plazos establecidos.

Diagrama 30. Ejemplo subdirectorio Dash

- **07_Insumos:** Materiales necesarios para la planificación, el análisis preliminar y la organización general del proyecto, con estudios previos, informes técnicos, mapas de referencia, bases de datos, documentos normativos y material logístico que orientaran el trabajo del equipo catastral en campo.

Diagrama 31. Ejemplo subdirectorio Insumos

  - **01_Cartografía_Básica:** Documentos cartográficos fundamentales para realizar el levantamiento de información, con mapas de delimitación territorial, identificación de límites políticos y administrativos, planos topográficos que permiten la correcta integración de la información espacial con los datos de campo. La cartografía básica también contiene planos de infraestructura existentes, redes viales, cuerpos de agua, y zonas de interés que serán utilizados como referencia en el proceso durante la recolección de datos y validación en terreno.

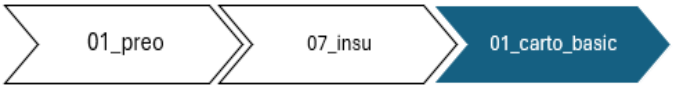

Diagrama 32. Ejemplo subdirectorio Cartografía Básica

- **01_Raster:** Datos cartográficos en formato ráster, los cuales son esenciales para el análisis geoespacial y la generación de productos cartográficos, con archivos como ortofotos, imágenes satelitales, mapas de elevación, y otros tipos de datos que permitan obtener una representación precisa del terreno. Estos datos son empleados para la visualización del área de estudio, identificación de características del terreno, pendientes y elevaciones para la actualización y validación de la información obtenida en campo.

Diagrama 33. Ejemplo subdirectorio Ráster

- **01_Orto:** Imágenes satelitales de alta resolución, especialmente las ortofotos, que son imágenes georreferenciadas que proporcionan una representación precisa del terreno, corregida para que la escala de las imágenes sea uniforme en toda la zona. Estas imágenes permiten identificar las características geográficas y urbanísticas del área en estudio, ya que ofrecen una referencia visual precisa que se puede combinar con otros datos geoespaciales para mayor exactitud de la información recolectada.

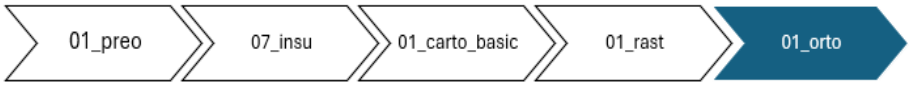

Diagrama 34. Ejemplo subdirectorio Ortofotos

  - **01_Urbano:** Ortofotos específicas para zonas urbanas a diferentes escalas, proporcionando imágenes satelitales que permiten analizar el área urbana. De esta manera, se puede identificar y mapear infraestructuras, como edificios, calles, parques, redes viales, etc., con el fin de lograr una planificación urbana y actualización catastral.

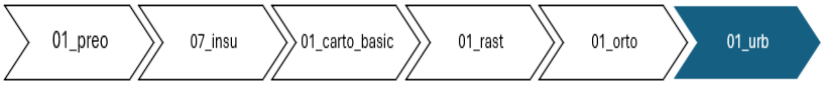

Diagrama 35. Ejemplo subdirectorio Urbano

  - **01_Rural:** Ortofotos específicas para zonas rurales a diferentes escalas, proporcionando imágenes satelitales que permiten analizar el área rural. De esta manera, se puede identificar características geográficas y físicas del terreno, como cultivos, cuerpos de agua, caminos rurales, límites de parcelas para la delimitación y clasificación del suelo, con el fin de facilitar tanto la validación de la información obtenida en campo como la actualización del catastro rural.

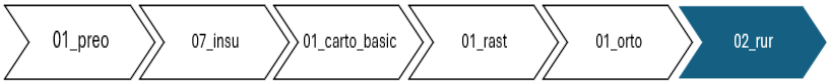

Diagrama 36. Ejemplo subdirectorio Rural

- **02_DTM:** Modelos Digitales de Terreno, que son representaciones tridimensionales (3D) del terreno. Estos proporcionan información precisa sobre la forma del terreno (relieve) sin incluir elementos como edificios o vegetación. Son esenciales para estudiar variaciones en la elevación del suelo, identificando pendientes, cuencas hidrográficas y elementos del relieve que pueden influir en la planificación catastral y desarrollo de infraestructuras.

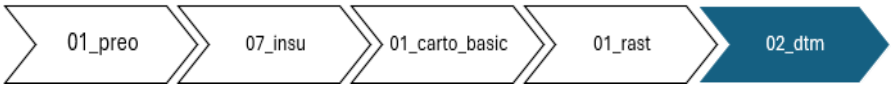

Diagrama 37. Ejemplo subdirectorio DTM

  - **01_Urbano:** Modelos Digitales de Terreno aplicados a zonas urbanas, excluyendo edificaciones y vegetación, lo que permite analizar las variaciones topográficas de áreas como calles, plazas, espacios públicos y privados dentro del entorno urbano. También se emplean para la gestión de riesgos, como inundaciones o desplazamientos de tierra y para urbanización y expansión.

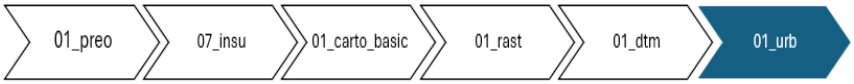

Diagrama 38. Ejemplo subdirectorio Urbano

  - **02_Rural:** Modelos Digitales de Terreno aplicados a zonas rurales, representando el relieve del terreno en áreas no urbanizadas, como campos agrícolas, bosques, ríos y zonas de montañas. También son empleados para la gestión del uso del suelo, permitiendo evaluar la topografía del terreno, identificar pendientes, cuencas hidrográficas y áreas susceptibles de erosión para la planificación territorial.

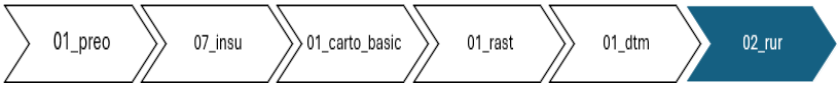

Diagrama 39. Ejemplo subdirectorio Rural

- **02_Vector:** Datos vectoriales, que se componen de elementos geoespaciales representados como puntos, líneas y polígonos. Representan de manera precisa las características geográficas y atributos espaciales de un territorio, como límites de propiedad, redes viales, etc. Los puntos representan ubicaciones exactas, como puntos de control geodésico, las líneas para definir rutas o fronteras, como carretas, caminos, etc., y los polígonos para representar áreas cerradas, como parcelas de terreno, zonas de uso especifico, etc.

Diagrama 40. Ejemplo subdirectorio Vector

- **01_Urbano:** Datos vectoriales referentes a áreas urbanas, que incluye representación de elementos geográficos urbanos como lotes de propiedad, calles, avenidas, edificaciones, zonas comerciales, etc., para el desarrollo urbano.

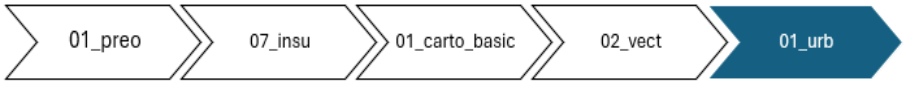

Diagrama 41. Ejemplo subdirectorio Urbano

- **02_Rural:** Datos vectoriales referentes a áreas rurales, que incluye representación de elementos geográficos rurales como parcelas de terreno, límites de propiedades, caminos rurales, cuerpos de agua, zonas de cultivo, para la gestión y planificación rural.

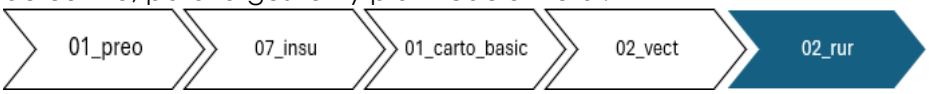

Diagrama 42. Ejemplo subdirectorio Rural

- **02_Estudios_Agrologia_Cartografía:** Estudios y documentos técnicos relacionados con el uso del suelo, la clasificación de tierras y todos los aspectos geográficos y agronómicos necesarios para el levantamiento de información en áreas rurales y agrícolas. Se encuentran informes sobre la capacidad del uso del suelo, identificando tierras aptas para diferentes tipos de cultivo, productividad agrícola, tipos de suelos, zonas de conservación y cartografía especifica que mapea zonas agrícolas, pastizales, bosques y zonas protegidas.

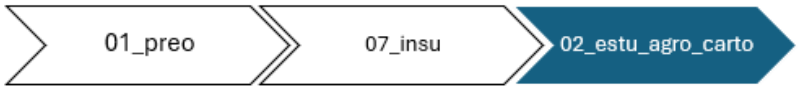

Diagrama 43. Ejemplo subdirectorio Estudios Agrología Cartografía

  - **01_Caracterizacion_Municipio:** Compila información como aspectos geográficos, socioeconómicos, demográficos, políticos y culturales, en conjunto sobre condiciones de infraestructura existente, aspectos legales y normativa local, adaptado a las particularidades del territorio y aspectos que impactan directamente la planificación y ejecución del proceso.

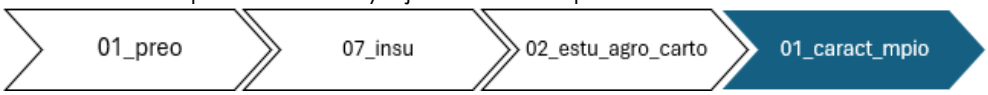

Diagrama 44. Ejemplo subdirectorio Caracterización Municipio

  - **02_AHT (Áreas Homogéneas de Tierras):** Identifican y delimitan las áreas de uso agrícola o rural dentro del municipio. Se refiere a zonas rurales con condiciones parecidas en términos de clima, topografía, material de origen y propiedades internas de los terrenos, que indican la capacidad productiva de la tierra a través de un valor potencial. Estas delimitaciones territoriales son el instrumento fundamental para llevar a cabo los avalúos catastrales en masa a escala rural.

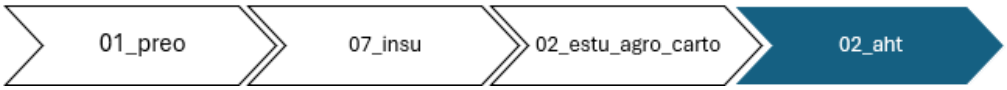

Diagrama 45. Ejemplo subdirectorio Áreas Homogéneas de Tierras

- **03_Leyendas:** Símbolos, colores y abreviaturas empleados en los mapas o planos, generados como herramientas para la correcta interpretación de la información cartográfica y geoespacial. Los símbolos gráficos representan diversas características geográficas o infraestructura, como áreas urbanas y rurales, así como zonas de uso del suelo. Los colores se utilizan para distinguir entre diferentes áreas y categorías de información. La abreviatura se emplea para representar elementos complejos como tipos de propiedad, categorías de terrenos, etc.

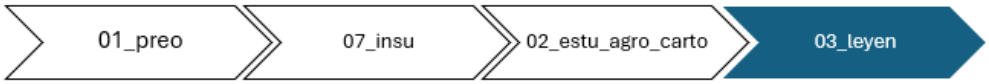

Diagrama 46. Ejemplo subdirectorio Leyendas

- **03_Informacion_Catastral:** Verificar la coherencia entre el catastro existente y la información recolectada, asegurando una representación actualizada de la realidad territorial. Abarca información sobre la ubicación, extensión y límites de las propiedades, uso del suelo, edificaciones existentes y áreas protegidas, entre otros. Estos datos se emplean para modificar propuestas o implementar cambios en el catastro actual, como resultado de análisis comparativos, actualizaciones de datos o la inclusión de nuevas construcciones.

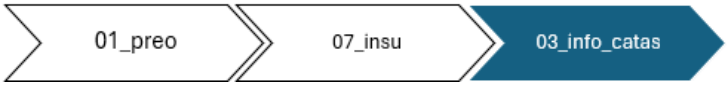

Diagrama 47. Ejemplo subdirectorio Información Catastral

- **01_R1_y_R2:** Son bases de datos alfanuméricas que incluyen datos físicos, legales y financieros sobre los terrenos de un municipio. Estos archivos se recolectan de dos formas diferentes. El primer registro (R1) incluye toda la información relacionada con la identificación, localización, tamaño, uso económico y valor del terreno, junto con los datos del supuesto dueño. En cambio, el segundo registro (R2) recolecta datos vinculados con el folio de inscripción en el registro de bienes raíces vinculado a cada cédula catastral, además de las particularidades específicas de las construcciones halladas en cada terreno.

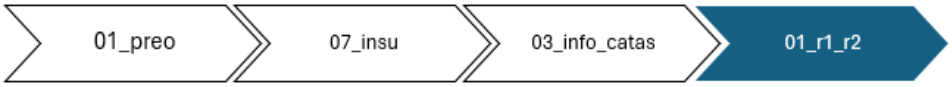

Diagrama 48. Ejemplo subdirectorio primer y segundo nivel

- **02_GDB:** Base de datos espaciales que contiene toda la información geográfica como zonas geográficas, límites territoriales, predios, parcelas, infraestructura, etc., que organiza y gestiona los datos obtenidos en campo. De esta forma el análisis de la información geográfica permite generar reportes visuales, manteniendo actualizado el catastro.

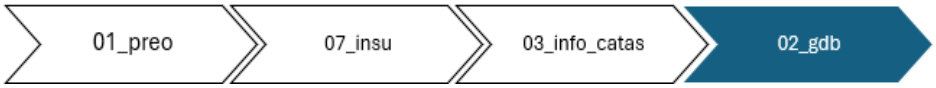

Diagrama 49. Ejemplo subdirectorio Geodatabase

- **03_Tablas_terreno_construccion (Vigentes):** Datos sobre terrenos y construcciones vigentes, como ubicación, uso, área, características de las edificaciones existentes. De esta forma se puede hacer un análisis sobre la distribución y uso del suelo, para la planificación urbana y desarrollo sostenible del área.

Diagrama 50. Ejemplo subdirectorio Tabla Terreno Construcción vigentes

- **04_Estudios_ZHF_y_ZHG (Vigentes):** Estudio de las zonas homogéneas físicas y las zonas homogéneas geoeconómicas. Las ZHF son áreas con características geográficas similares, como el relieve, la topografía y las condiciones del terreno, mientras que las ZHG agrupan territorios con características socioeconómicas y de uso del suelo semejantes.

Diagrama 51. Ejemplo subdirectorio Estudio ZHF y ZHG vigentes

- **04_Deslindes:** Documentos que contienen los límites del territorio a catastrar, así como los procesos legales necesarios para garantizar una delimitación de las propiedades y evitar conflictos de propiedad. Cuenta con estudios, mapas y registros oficiales de los limites municipales, así como la validación y resolución de cualquier disputa territorial. Además, se especifican los límites de un terreno, donde los propietarios, ya sea por mutuo acuerdo o mediante un proceso jurídico, reconocen los límites de propiedad. Los documentos asociados a este proceso incluyen la identificación de los titulares de derechos reales, el número predial, el certificado de tradición y libertad, entre otros.

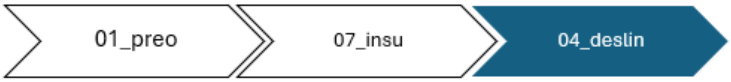

Diagrama 52. Ejemplo subdirectorio Deslindes

- **01_Shape file:** Se trata de un formato vectorial utilizado para la conservación de datos espaciales, en el que se registran las coordenadas geográficas de los elementos, así como los atributos vinculados a los mismos. El formato puede constar de un número variable de archivos, pero como requisito mínimo debe incluir al menos tres archivos con extensiones ".shp", ".shx" y ".dbf". Normalmente, contiene extensiones: ".cpg", ".dbf", ".prj", ".sbn", ".sbx", ".shp" y ".shx".

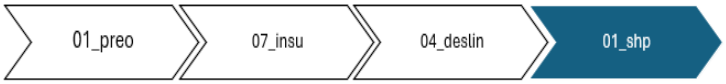

Diagrama 53. Ejemplo subdirectorio Shape file

- **02_Acta_deslinde:** Certifican los deslindes, presentados entre propietarios de terrenos o con entidades gubernamentales, definiendo de manera oficial los límites de las propiedades involucradas, asegurando la correcta integración de estos en el proceso catastral. El documento contiene puntos de discusión y el

acuerdo para la implementación para todas o solo las reuniones del proceso de delimitación.

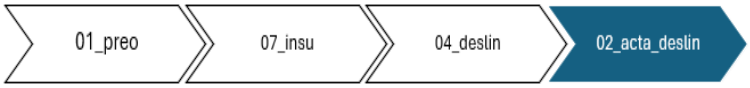

Diagrama 54. Ejemplo subdirectorio Acta Deslinde

- **03_Acto_Administrativo:** Validan y formalizan los deslindes y la delimitación de terrenos mediante una resolución emitida, la cual otorga validez oficial a los límites establecidos entre propiedades. Estos documentos aseguran que los procesos de delimitación se registren correctamente en el sistema, proporcionando una base legal sólida y garantizando el reconocimiento por parte de las autoridades y su vinculación legal.

Diagrama 55. Ejemplo subdirectorio Acto Administrativo

- **05_Perimetro:** Define el límite físico del suelo, determinando su área mediante una línea imaginaria continua que separa el suelo urbano del rural, así como el suelo urbano en expansión. Estos documentos establecen los límites del área a catastrar y regulan el ordenamiento territorial, con el fin de definir con precisión las fronteras del territorio basados en la normatividad y directrices legales.

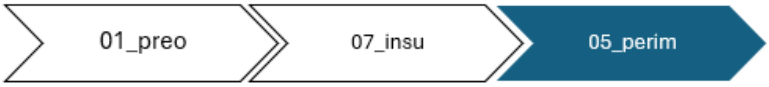

Diagrama 56. Ejemplo subdirectorio Perímetro

  - **01_Certificado_uso_suelo:** Certificados oficiales que validan el uso permitido del suelo en un predio o edificación dentro de las zonas urbanas o rurales, según la normativa vigente. Se garantiza que el uso del terreno se ajuste a los planes urbanísticos, ambientales y de desarrollo del municipio, respaldando legalmente las actividades que se realicen.

Diagrama 57. Ejemplo subdirectorio Certificado uso del suelo

  - **02_Certificado_instrumento_vigente:** Documentos que validan los instrumentos legales y normativos vigentes relacionados con el uso del suelo, como los planes de ordenamiento territorial y demás regulaciones urbanísticas.

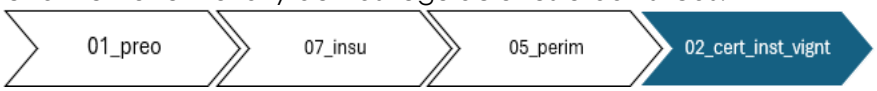

Diagrama 58. Ejemplo subdirectorio Certificado instrumento vigente

  - **03_Analisis:** Revisión especifica y evaluación de los límites geográficos de un terreno, así como el análisis de las normativas que afectan el catastro y el uso del suelo, necesarios para la planificación y ejecución del levantamiento de

información, permitiendo conocer las condiciones territoriales y legales del área objeto de estudio.

Diagrama 59. Ejemplo subdirectorio Análisis

- **06_Insumos_Registrales:** Documentos, registros y datos legales necesarios para el proceso catastral, que certifican propiedad de los terrenos, validando así la titularidad de estos. Proporciona la base legal de los derechos de propiedad, contribuyendo a la resolución de posibles disputas y al registro de títulos de propiedad.

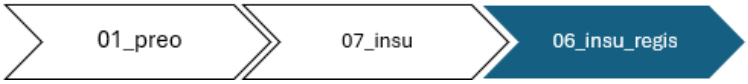

Diagrama 60. Ejemplo subdirectorio Insumos Registrales

- **07_Insumos_Fuentes_Secundarias:** Datos, informes o materiales obtenidos de estudios previos, investigaciones externas, que proporcionan contextos adicionales y ayudan a validar, ampliar o corregir los datos recolectados durante el proceso.

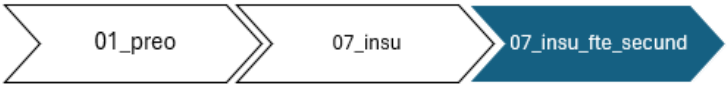

Diagrama 61. Ejemplo subdirectorio Insumos Fuentes Secundarias

- **08_Instrumento_Ordenamiento_Territorial:** Documentos, mapas y planes específicos relacionados con la clasificación, delimitación y registro de propiedades y terrenos del municipio. Estos elementos, en concordancia con las políticas de planificación urbana y rural, servirán como guía para el levantamiento catastral, en cumplimiento de las regulaciones territoriales del municipio. que de acuerdo con las políticas de planificación urbana y rural permitirá guiar el levantamiento catastral dentro del marco de las regulaciones territoriales del municipio.

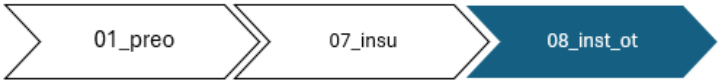

Diagrama 62. Ejemplo subdirectorio Instrumento Ordenamiento Territorial

- **09_Saldos_Conservacion:** Registros detallados sobre el estado de conservación de los territorios. Refleja el historial de cambios y ajustes aplicados en cada área, documentos que proporcionan información sobre la preservación de los recursos naturales, intervenciones realizadas para conservar el entorno y modificaciones relevantes para la actualización catastral.

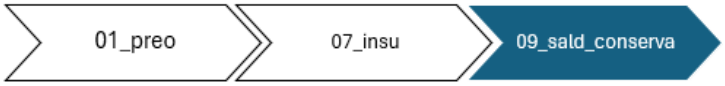

Diagrama 63. Ejemplo subdirectorio Saldos de Conservación

- **10_CICA_App:** Herramientas especificas diseñadas para la recolección, procesamiento y análisis de datos catastrales, permitiendo la integración de diferentes fuentes de datos, la georreferenciación y el análisis detallado de la información del terreno y las propiedades, cumpliendo con los estándares y normativas aplicables en el proceso de gestión catastral.

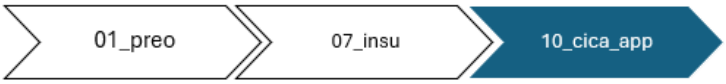

Diagrama 64. Ejemplo subdirectorio CICA App

- **11_Componente_Social:** Información relevante sobre los aspectos sociales del proceso, abordando la identificación y clasificación de los actores sociales afectados. Esto facilita la interacción con la comunidad y permite atender sus necesidades y preocupaciones sociales durante la ejecución del proyecto. Además, se gestionan los aspectos humanos y sociales, promoviendo la participación y el entendimiento entre las partes involucradas.

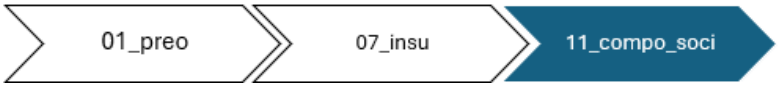

Diagrama 65. Ejemplo subdirectorio Componente Social

  - **01_Identificacion_Social_Territorio.pdf:** Documento que identifica los grupos sociales, comunidades y actores territoriales dentro del área a catastrar. Este proporciona un análisis de las diversas poblaciones y entidades que pueden verse afectadas por el proceso catastral, con un enfoque adecuado para la participación y consulta de las comunidades en el proyecto.

Diagrama 66. Ejemplo subdirectorio Identificación Social del Territorio

  - **02_Mapa_actores.xls:** Mapa o listado en formato Excel de los actores sociales identificados en el área a catastrar. Este documento organiza y presenta la información relevante sobre los distintos actores sociales, como comunidades, organizaciones locales y otros grupos que tienen impacto o interés en el proceso. Su formato en Excel facilita la manipulación y actualización de los datos, y permite un análisis eficiente de la distribución y clasificación de estos actores.

Diagrama 67. Ejemplo subdirectorio Mapa Actores

- **08_Contratos_Personal:** Contratos relacionados con el personal que trabajará en el levantamiento catastral. Contiene información sobre acuerdos laborales de los empleados encargados de las actividades de campo y otras tareas operativas dentro del proceso. Estos contratos incluyen términos de trabajo, responsabilidades, duración, honorarios, y demás detalles legales que formalizan la relación laboral de los involucrados.

Diagrama 68. Ejemplo subdirectorio Contratos Personal

  - **01_IGAC:** Contratos del personal directamente contratado o asignado por el IGAC para participar en el proceso catastral. Este documento incluye los contratos de los empleados del IGAC que tienen una función específica en el levantamiento catastral.

Se incluye detalles sobre el rol de cada persona, las condiciones laborales, el tiempo de duración del contrato, y aspectos legales relacionados con su participación.

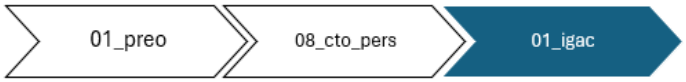

Diagrama 69. Ejemplo subdirectorio IGAC

- **02_Operador:** Contratos con operadores privados o terceros que han sido contratados para realizar tareas específicas dentro del proceso de levantamiento catastral. Se incluye detalles sobre el rol de cada persona, las condiciones laborales, el tiempo de duración del contrato, y aspectos legales relacionados con su participación.

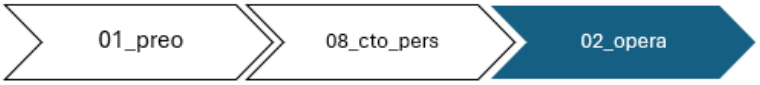

Diagrama 70. Ejemplo subdirectorio Operador

De acuerdo con lo anterior, en la siguiente imagen se presenta las características de cada producto:

Dir_1	Dir_2	Dir_3	Dir_4	Dir_5	Dir_6	Contenido	Dir_7	Dir_8	Dir_9
19/11/2024 VERSIÓN 1	DEPARTAMENTO	MUNICIPIO	FUENTES DE FINANCIACION	01_Preoperativos	01_Propuesta	01_Documento (Propuesta)	AAAAMMDD_prop_tecn_econ.pdf		
						02_Terminos_de_Referencia	AAAAMMDD_termn_ref.pdf		
					02_Carta_Aceptacion	AAAAMMDD_carta_accept.pdf			
					03_Contrato_y_Modificaciones	AAAAMMDD_cto_modif.pdf			
					04_Acta_Inicio	AAAAMMDD_acta_ini.pdf			
					05_Plan_Gestion_Proyectos	01_Plan_Operativo	AAAAMMDD_crono.xlsx		
							AAAAMMDD_matriz_riesg.xlsx		
							AAAAMMDD_plan_opera.docx		
							AAAAMMDD_uit_urb.zip		
							AAAAMMDD_uit_rur.zip		
							AAAAMMDD_analis_crg_trab.zip		
						02_Plan_Gestion_Integral ***(El enlace carga el plan)***	AAAAMMDD_plan_compo_interloc.docx		
							AAAAMMDD_plan_comuni.docx		
							AAAAMMDD_plan_comuni_publi.docx		
							AAAAMMDD_plan_econo.docx		
							AAAAMMDD_plan_gest_intgrl.docx		
						03_Plan_Calidad	AAAAMMDD_plan_calid.docx		
							AAAAMMDD_matriz_comuni_part_intere.xlsx		
							AAAAMMDD_compet_perf_pers.xlsx		
							AAAAMMDD_ident_analis_enrada_plan_calid.xlsx		
						04_Plan_Gestion_Ambiental	01_PGAS (Plan de Gestion Ambiental y social)	AAAAMMDD_pgas.docx	
							02_MGAS (Marco de Gestion Ambiental y social)	AAAAMMDD_mgas.docx	
				06_Pre-Reconocimiento	01_Diagnostico	01_Preliminar (Basico / Caracterizacion)	AAAAMMDD_caract_catas.docx		
						02_Catastral	AAAAMMDD_diag_catas.docx		
					02_Marcas	01_Consolidacion	01_urb	AAAAMMDD_marca_urb.xlsl	
							02_rur	AAAAMMDD_marca_rur.xlsx	
					03_Fuente_Espacial	01_GDB	AAAAMMDD_analis_precono.gdb		
						02_MPK	01_urb	AAAAMMDD_analis_prerecono_urb.mpk	
							02_rur	AAAAMMDD_analis_prerecono_rur.mpk	
					04_Dashboard	01_Dash	AAAAMMDD_dash.xlsx		
				07_Insumos	01_Cartografia_Basica	01_Raster	01_Orto	01_urb	orto10_XXX_AAAAMMDD.zip
								02_rur	orto100_XXX_AAAAMMDD.zip
							02_DTM	01_urb	mdt1_divipola_AAAAMMDD.zip
								02_rur	mdt10_divipola_AAAAMMDD.zip
						02_Vector	01_urb	carto2000_divipola_rs_AAAAMMDD.zip	
							02_rur	carto10000_divipola_rs_AAAAMMDD.zip	
					02_Estudios_Agrologia_Cartografia	01_Caracterizacion_Municipio	AAAAMMDD_caract_terri_mun		
						02_AHT (Areas Homogeneas de Tierras)	AAAAMMDD_aht.zip		
						03_Leyendas	AAAAMMDD_leyen_aht.pdf		
					03_Informacion_Catastral	01_R1_y_R2	AAAAMMDD_r1.xlsx		
							AAAAMMDD_r2.xlsx		
						02_GDB	AAAAMMDD_divipola.gdb		
						03_Tablas_terreno_construccion (Vigentes)	AAAAMMDD_tab_terre_constr_urb.xlsx		
							AAAAMMDD_tab_terre_constr_urb_z1.xlsx		
							AAAAMMDD_tab_terre_constr_rur.xlsx		
						04_Estudios_2HF_y_2HG (**Vigentes**)	AAAAMMDD_zhf_zhg.pdf		
							AAAAMMDD_memo_avalu_pto_invest.pdf		
							AAAAMMDD_estim_precio.pdf		
					04_Deslindes	01_Shape file	AAAAMMDD_limi.zip		
						02_Acta_deslinde	AAAAMMDD_acta_deslin_XXX.pdf		
						03_Acto_Administrativo	AAAAMMDD_acto_admin_XXX.pdf		
					05_Perimetro	01_Certificado_uso_suelo	AAAAMMDD_cert_uso_suelo.pdf		
						02_Certificado_instrumento_vigente	AAAAMMDD_cert_instr_vig_XXX.pdf		
						03_Analisis	AAAAMMDD_analis.pdf		
					06_Insumos_Registrales	AAAAMM_snr_hist.xlsx			
					07_Insumos_Fuentes_Secundarias	AAAAMMDD_entidad_XXX.zip			
						AAAAMMDD_entidad1_XXX.zip			
						AAAAMMDD_entidad2_XXX.zip			
					08_Instrumento_Ordenamiento_Territorial	AAAAMMDD_eot_XXX.pdf			
						AAAAMMDD_doc1.pdf			
						AAAAMMDD_doc2.pdf			
					09_Saldos_Conservacion	AAAAMMDD_invet_sald.xls			
					10_CICA_App	AAAAMMDD_infor_cica_app.pdf			
					11_Componente_Social	01_Caracterizacion_Social_Ambiental.pdf	AAAAMMDD_ident_soci_amb_terri.pdf		
						02_Mapa_Actores.xls	AAAAMMDD_mapa_actor.xlsx		
				08_Contratos_Personal	01_IGAC	AAAAMMDD_cto_pers_igac.pdf			
					02_Operador	AAAAMMDD_cto_pers_XXX.pdf			

Imagen 1. Etapa Preoperativa.

Para la Etapa Operativa se tiene:

- **01_Resolucion_de_Apertura:** Contiene los documentos legales y administrativos que formalizan el inicio del proceso de levantamiento catastral.

Diagrama 71. Ejemplo subdirectorio Resolución de Apertura

  - **01_Resolucion_de_Apertura:** Resolución firmada que da inicio a la etapa operativa del levantamiento catastral en el municipio. En este documento se especifican varios detalles, como fecha de inicio de actividades, el alcance territorial del levantamiento, la designación del responsable del proceso y las normativas legales que regulan la ejecución del proceso. Esta resolución marca formalmente el comienzo del levantamiento de información, proporcionando el marco legal y administrativo para la ejecución del proyecto en la zona determinada.

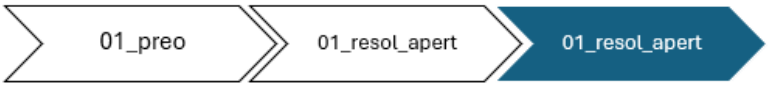

Diagrama 72. Ejemplo subdirectorio Resolución de Apertura

  - **02_Publicacion_Diario_Oficial:** Archivos PDF o imagen de la publicación que establece formalmente el inicio de las operaciones catastrales, detallando la resolución correspondiente y su número de registro, además de la notificación pública dirigida a la comunidad con el fin de asegurar que tanto los propietarios de bienes como las autoridades locales estén informados sobre el inicio de la recolección de datos.

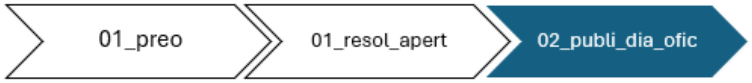

Diagrama 73. Ejemplo subdirectorio Publicación Diario Oficial

  - **03_Oficios_Comunicacion:** Cartas formales dirigidas a las autoridades locales, entidades del municipio incluyendo los oficios dirigidos a la alcaldía para informar sobre el levantamiento catastral, así como los oficios a otros actores sociales con el fin de notificar a las organizaciones sociales y comunitarias sobre las actividades catastrales.

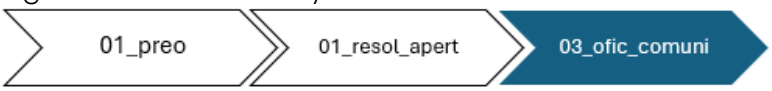

Diagrama 74. Ejemplo subdirectorio Oficios Comunicación

- **02_Componente_Social:** Su objetivo es garantizar una adecuada socialización del proceso catastral, promoviendo la participación de los actores clave, y asegurar que los derechos de la población sean respectados durante la recolección de información en campo. Gestiona todo lo relacionado con la interacción con las comunidades, actividades de sensibilización y coordinación que permitan desarrollar el levantamiento catastral.

Diagrama 75. Ejemplo subdirectorio Componente Social

- **01_Nivel_de_Interlocución_0 (Acercamiento Regional):** Actividades iniciales de contacto y establecimiento de relaciones con las comunidades y autoridades locales. Su objetivo es facilitar el proceso de recolección de datos y aseguran que las comunidades entiendan el objetivo y la importancia del levantamiento catastral.

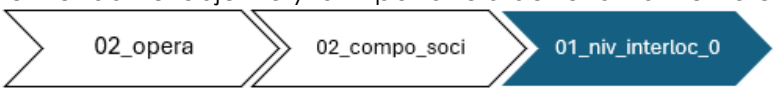

Diagrama 76. Ejemplo subdirectorio Nivel de Interlocución 0

  - **01_Informes:** Informes detallados de las reuniones iniciales con líderes de comunidades, autoridades locales y otros actores clave, en los cuales se explica el proceso catastral. Además, se especifica las actividades de sensibilización realizadas a la comunidad en donde se explica la importancia del levantamiento catastral, así como también los compromisos alcanzados durante las reuniones con las comunidades o autoridades locales, acceso a propiedades y recolección de datos.

Diagrama 77. Ejemplo subdirectorio Informe

  - **02_Registro_fotografico:** Imágenes tomadas durante las actividades de acercamiento y socialización. Se incluyen fotografías de reuniones con las comunidades y autoridades, espacios donde se realizaron talleres o presentaciones informativas y de propiedades o sitios en los que llevo a cabo la ejecución del levantamiento catastral.

Diagrama 78. Ejemplo subdirectorio Registro Fotográfico

  - **03_Listas_Asistencia:** Listas de participantes en talleres o reuniones informativas de todas las actividades relacionadas con la socialización o sensibilización del proceso catastral, donde los asistentes firman para dejar constancia de su participación.

Diagrama 79. Ejemplo subdirectorio Lista Asistencia

  - **04_Difusión:** Materiales como folletos, carteles, volantes, correos, publicaciones en redes sociales, páginas web o comunicados de prensa emitidos por el IGAC o autoridades locales que se distribuyen para explicar el proceso catastral y el desarrollo que va a traer para la población como también convocatorias públicas en las que se invita a la comunidad a participar en reuniones informativas para el desarrollo del proceso catastral.

Diagrama 80. Ejemplo subdirectorio Difusión

- **02_Nivel_de_Interlocución_I (Institucional/Comunitaria):** Documentación relacionada con las interacciones y colaboraciones con las entidades institucionales y las comunidades. Documentos que se encuentran: Identificación social actualizada, Documento de mapa de actores actualizado, Informe de interlocución comunitaria (formato Informe interlocución comunitaria) y diligenciamiento de un registro de asistencia (Formato asistencia espacios comunitarios). Se coordina acciones, resuelven dudas para un buen desarrollo del levantamiento catastral. Deberán ser suministrados en formato PDF, JPG, MP4, entre otros.

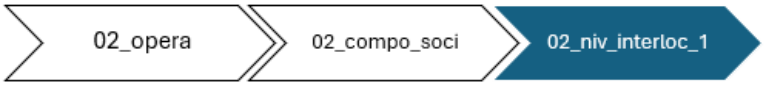

Diagrama 81. Ejemplo subdirectorio Nivel de Interlocución 1

- **01_Informes:** Informes de reuniones institucionales que lleven un registro destallado de las conversaciones sostenidas con alcaldía, gobernación, secretaría de Planeación. Se incluyen los acuerdos alcanzados, puntos tratados y acciones que aseguren el avance del proceso catastral. Así mismo, informes de sensibilización comunitaria, documentando actividades realizadas para explicar a la población la importancia del proceso catastral.

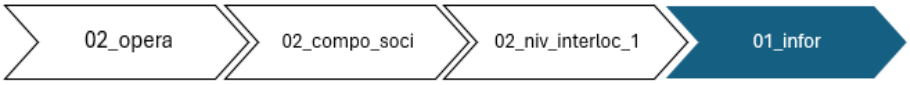

Diagrama 82. Ejemplo subdirectorio Informes

- **01_Cartografia:** Mapas generados o utilizados durante las actividades de interlocución social, que muestran los límites territoriales, distribución de propiedad, sectores involucrados o cualquier cartografía usada para ilustrar procesos o resultados del levantamiento catastral en las reuniones con la comunidad. Debe incluir documentos físicos como archivos digitales en formatos vectoriales (shapefile, GDB) o ráster (Ortofotos) en donde se evidencia de forma precisa el área de influencia de la intervención.

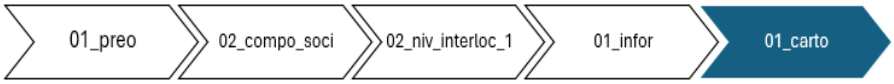

Diagrama 82. Ejemplo subdirectorio Cartografía

- **02_Registro_fotografico:** Imágenes que dan cuenta de las actividades realizadas en el terreno, reuniones o talleres de socialización que permitan verificar el desarrollo del proceso, además que sirve para documentar las visitas a los predios, registro de las condiciones de los límites y puntos de referencia.

Diagrama 83. Ejemplo subdirectorio Registro Fotográfico

- **03_Listas_Asistencia:** Registros de asistencia a reuniones con autoridades como a los talleres donde se capacita a la comunidad sobre el proceso catastral. Debe reflejar presencia de funcionarios gubernamentales, propietarios de predios y líderes sociales que han sido informados sobre el proceso.

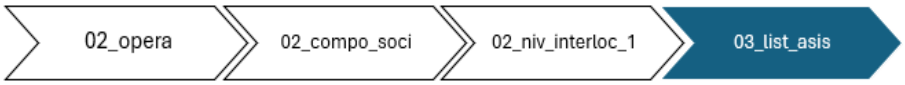

Diagrama 84. Ejemplo subdirectorio Listas Asistencia

- **04_Difusión:** Materiales como folletos, carteles, volantes, correos, publicaciones en redes sociales, páginas web o comunicados de prensa emitidos por el IGAC o autoridades locales que se distribuyen para explicar el proceso catastral y el desarrollo que va a traer para la población como también convocatorias públicas en las que se invita a la comunidad a participar en reuniones informativas para el desarrollo del proceso catastral.

Diagrama 85. Ejemplo subdirectorio Difusión

- **03_Nivel_de_Interlocución_2 (Lideres):** Abarca todo el trabajo que se realiza con los lideres comunitarios, quienes desempeñan un papel importante de socialización en el levantamiento catastral. Los lideres no solo informan, sino que también participan activamente en la resolución de problemas y en la organización de actividades de campo, por ende, la necesidad de documentar detalladamente todas las interacciones con estos actores. Deberán ser suministrados en formato PDF, JPG, MP4, entre otros.

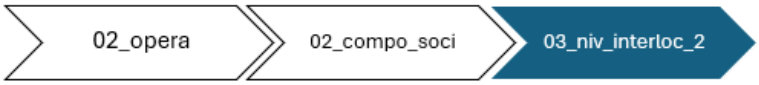

Diagrama 86. Ejemplo subdirectorio Nivel de Interlocución 2

- **01_Informes:** Informes sobre reuniones realizadas con los lideres de las comunidades o las organizaciones sociales que representan a los propietarios de los predios catastrales. Cada informe debe contener un resumen de los discutido en las reuniones, incluyendo las preocupaciones planteadas por los lideres, las estrategias de socialización utilizadas, las aclaraciones sobre el proceso y los acuerdos alcanzados. De esta forma se lleva un seguimiento del proceso catastral.

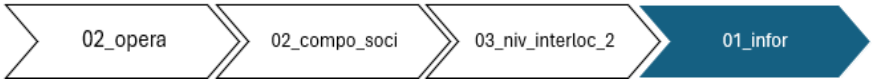

Diagrama 87. Ejemplo subdirectorio Informes

- **02_Registro_Fotografico:** Imágenes que dan cuenta de las actividades realizadas en el terreno, reuniones o talleres de socialización que permitan verificar el desarrollo del proceso, además que sirve para documentar las visitas de campo donde los líderes intervienen y se tiene conocimiento de las áreas específicas que están siendo catastradas.

Diagrama 88. Ejemplo subdirectorio Registro Fotográfico

- **03_Listas_Asistencia:** Registros de todas las personas que participaron en las actividades de socialización y sensibilización dirigidas a los lideres comunitarios,

sea en talleres o reuniones. Estas listas deben contener nombres completos, identificaciones y firmas de los participantes, junto con el cargo o rol que desempeñan dentro de la comunidad.

Diagrama 89. Ejemplo subdirectorio Lista Asistencia

- **04_Difusión:** Materiales como folletos, carteles, volantes, correos, publicaciones en redes sociales, páginas web o comunicados de prensa emitidos por el IGAC o autoridades locales que se distribuyen para explicar el proceso catastral y el desarrollo que va a traer para la población como también convocatorias públicas en las que se invita a la comunidad a participar en reuniones informativas para el desarrollo del proceso catastral.

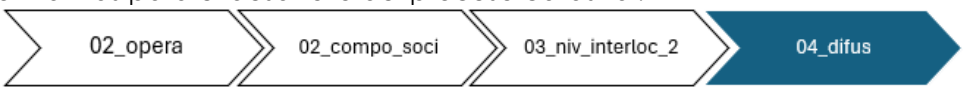

Diagrama 90. Ejemplo subdirectorio Difusión

- **04_Nivel_de_Interlocución_3 (JAL y Comunidad):** Los documentos deben contener el informe de interlocución comunitaria con un registro de las actividades adelantadas y un análisis consolidado de la retroalimentación recibida pertinente para la operación en campo que, a su vez, contenga: Informe de la metodología adelantada en los talleres con las personas que adelantarán la tarea de recolección de información y los principales resultados, cronograma de la operación en campo con la participación de la comunidad y acompañamiento del operador, cronograma y estrategia de comunicaciones, Identificación de conflictividades y su respectiva estrategia de abordaje implementada, en las primeras Unidades de Intervención se espera la consolidación de recomendaciones y sugerencias para el mejor desarrollo de esta actividad en el resto del territorio y diligenciamiento de un registro de asistencia en el formato establecido para ello. Deberán ser suministrados en formato PDF, JPG, MP4, entre otros.

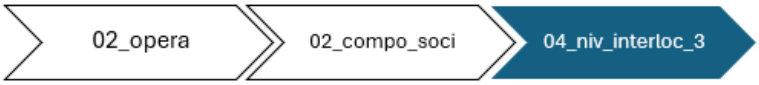

Diagrama 91. Ejemplo subdirectorio Nivel de Interlocución 3

- **01_Informes:** Detallan las actividades realizadas para socializar, sensibilizar y coordinar con las JAL y la comunidad durante el proceso de levantamiento catastral. Describe las actividades de sensibilización, especificando un resumen de los discutido en las reuniones, incluyendo las estrategias de socialización utilizadas, las aclaraciones sobre el proceso y los acuerdos alcanzados.

Diagrama 92. Ejemplo subdirectorio Informe

- **02_Registro_Fotografico:** Imágenes que documentan las actividades de socialización y las interacciones con las JAL y la comunidad. De esta manera se respalda la transparencia del proceso.

Diagrama 93. Ejemplo subdirectorio Registro Fotográfico

- **03_Lista_Asistencia:** Registros de asistencia a todas las actividades de socialización y coordinación realizadas con las JAL y la comunidad. Con estos registros se tiene constancia de quienes han sido informados y sensibilizados sobre el proceso catastral. Estos registros deben incluir nombres, firmas y datos de contacto de los participantes.

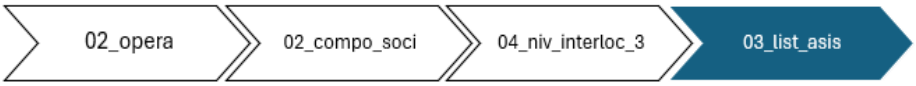

Diagrama 94. Ejemplo subdirectorio Lista Asistencia

- **04_Difusión:** Materiales como folletos, carteles, volantes, correos, publicaciones en redes sociales, páginas web o comunicados de prensa emitidos por el IGAC o autoridades locales que se distribuyen para explicar el proceso catastral y el desarrollo que va a traer para la población como también convocatorias públicas en las que se invita a la comunidad a participar en reuniones informativas para el desarrollo del proceso catastral.

Diagrama 95. Ejemplo subdirectorio Difusión

- **03_Componente_Fisico_Juridico:** Asegura que la información sobre los predios catastrales no solo sea exacta en términos de geolocalización, sino también en cuanto a la veracidad jurídica de la propiedad y uso del suelo. Almacena todos los documentos que validan y aprueban las bases catastrales, así como aquellos vinculados con la resolución de cualquier disputa sobre la propiedad o delimitación de los predios.

Diagrama 96. Ejemplo subdirectorio Componente Físico y Jurídico

  - **01_Base_Catastral_Aprobada:** Documentos que certifican que la base catastral ha sido revisada, validada y aprobada. Es el resultado final del trabajo en campo con la información validada durante la recolección de datos catastrales. La base catastral es un archivo alfanumérico que incluye detalles como el nombre del propietario, ubicación exacta, uso del suelo, dimensiones y delimitación geográfica precisa de cada predio. Este archivo se compone generalmente de dos partes: los registros alfanuméricos (datos del propietario, características del terreno, etc.) y la información geoespacial (coordenadas y limites precisos de cada predio).

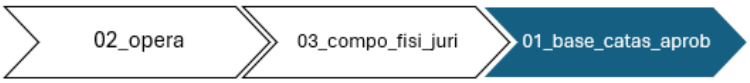

Diagrama 97. Ejemplo subdirectorio Base Catastral Aprobada

- **04_Componente_Económico:** Descripción de los métodos, fuentes y medición de la precisión del proceso para la determinación del avalúo catastral, ofertas de mercado inmobiliario, avalúos puntuales, especificación de modelos econométricos, modelos estadísticos, entre otros. Almacena documentos, informes y planificaciones relacionados con la asignación de recursos, que permite hacer seguimiento y control de costos. Estos documentos serán suministrados en sus formatos fuente xlsx, doc, pdf, etc.

Diagrama 98. Ejemplo subdirectorio Componente Económico

- **05_CC_Seguimiento:** Monitoreo y seguimiento de las actividades catastrales. Contiene todos los informes, indicadores de desempeño, cronogramas de ejecución y cualquier otro documento que permita verificar el avance del levantamiento catastral. Se lleva un registro detallado de las actividades realizadas en campo.

Diagrama 99. Ejemplo subdirectorio Seguimiento

  - **01_aaaammdd:** Permite la organización temporal de los documentos de seguimiento, proporcionando claridad sobre las fechas exactas de los informes y actualizaciones de avance del proceso, asegurando que los informes sean fácilmente accesibles.

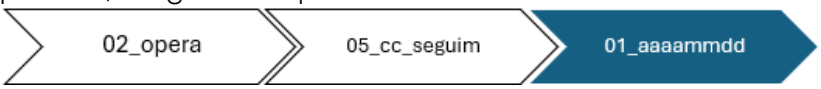

Diagrama 100. Ejemplo subdirectorio aaaammdd

    - **01_Hito:** Registra los puntos clave en el proceso catastral. Los hitos corresponden a eventos o actividades significativas que marcan avances sustanciales en la recolección y validación de datos, tales como la finalización de una fase especifica de trabajo en campo, el inicio de la validación de datos, o consolidación de información catastral de un área.

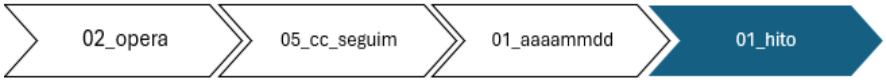

Diagrama 101. Ejemplo subdirectorio Hito

      - **01_Rural:** Registra los hitos alcanzados en las áreas rurales del municipio en proceso de levantamiento catastral. Información que incluye actividades como la medición de predios rurales, georreferenciación de marcas de delimitación de terreno, etc. Se registra cualquier ajuste realizado en el cronograma de actividades rurales y estudios de impacto que se hayan hecho durante el proceso.

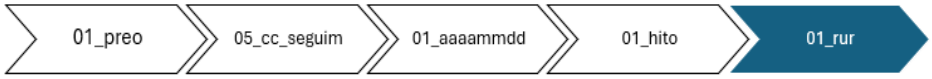

Diagrama 102. Ejemplo subdirectorio Rural

      - **02_Urbano:** Hitos alcanzados en las áreas urbanas del municipio en proceso de levantamiento catastral. Información correspondiente a los predios urbanos, que incluyen tanto la información catastral de edificios,

terrenos, como las construcciones existentes. Además de la georeferenciación de predios y estructuras se registra actividades de campo en zonas urbanas, la validación de datos y las actualizaciones que puedan haberse generado en cuánto los limites urbanos, áreas de expansión, o datos asociados a infraestructuras y servicios públicos.

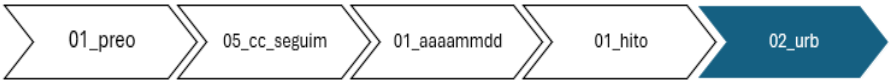

Diagrama 103. Ejemplo subdirectorio Urbano

- **03_Calidad:** Gestiona los documentos relacionados con los controles de calidad de la información recolectada en campo. Alberga informes de auditoría de calidad, procesos de verificación de datos y la validación final de la información catastral antes de su consolidación. Incluye informes de calidad relacionados con la precisión de los datos geoespaciales (coordenadas geográficas de los predios), la consistencia de los registros catastrales (tamaño, uso, valor de los terrenos) y los informes de las herramientas utilizadas para la validación de datos, como software ARCGis, ArcMap, etc., o bases de datos.

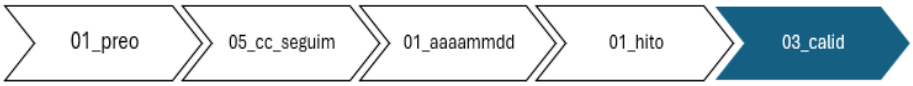

Diagrama 104. Ejemplo subdirectorio Calidad

- **06_Informes_Seguimiento:** Asegurar el monitoreo y control continuo del avance del proceso. Este documento abarca tanto el seguimiento de la calidad de la información recolectada como la correcta ejecución de los trabajos en campo. Los informes detallan el progreso de las actividades, identifican posibles desviaciones en el proceso y se proponen acciones correctivas cuando sea necesario.

Diagrama 105. Ejemplo subdirectorio Informes de seguimiento

  - **01_Calculadora_Seguimiento:** Hojas de cálculo o sistemas automatizados que permiten evaluar de manera continua los indicadores de progreso en tiempo real. Se gestionan los cálculos relativos a la cobertura territorial levantada, el número de predios verificados y todos los parámetros que permiten tener visibilidad sobre el alcance del proceso en cada municipio o zona catastral.

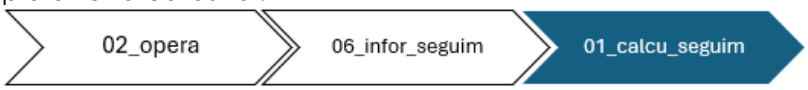

Diagrama 106. Ejemplo subdirectorio Calculadora Seguimiento

  - **02_Indicadores:** Medir el avance y la calidad del proceso catastral. De esta manera, proporciona mediciones precisas como el porcentaje de predios verificados, la cantidad de datos corregidos, terrenos con problemas de delimitación o el avance en la cobertura territorial, facilitando la toma de decisiones informadas.

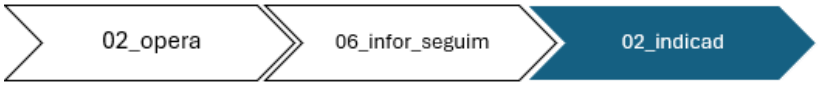

Diagrama 107. Ejemplo subdirectorio Indicadores

- **03_Formatos_Seguimiento (Control de calidad):** Formatos utilizados para realizar el seguimiento de control de calidad, tales como documentos estandarizados para el control de calidad de la información recolectada en campo, listas de verificación, matrices de validación de datos, formularios de auditoría y la coherencia con los registros alfanuméricos de los predios con los datos recolectados en campo.

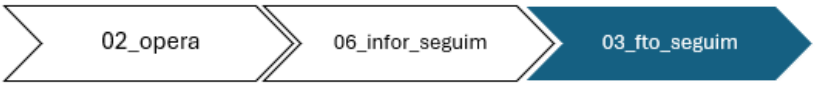

Diagrama 108. Ejemplo subdirectorio Formato Seguimiento control de calidad

- **04_Salvaguardas:** Respalda las medidas implementadas para garantizar que el proceso catastral se lleve a cabo con el cumplimiento de la normativa de protección social y ambiental, asegurando que no se generen impactos negativos durante la recolección de datos.

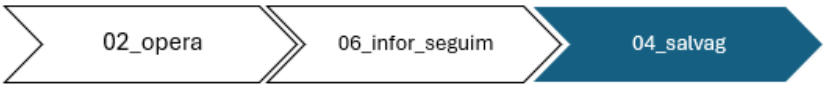

Diagrama 109. Ejemplo subdirectorio Salvaguardas

  - **01_Social:** Informes que contienen los resultados de consultas previas realizadas con las comunidades, comunicaciones establecidas con las autoridades locales y los mecanismos implementados para asegurar que las comunidades involucradas en el proceso catastral estén informadas.

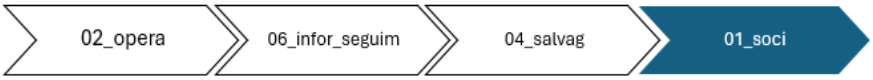

Diagrama 110. Ejemplo subdirectorio Social

    - **01_Informes:** Resultados de las reuniones con las comunidades, así como los documentos relacionados con la socialización del proceso catastral y su impacto social. Además, almacena las actas de las consultas realizadas con las comunidades, con el fin de garantizar el cumplimiento de los estándares de participación social.

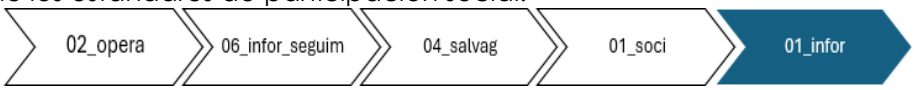

Diagrama 111. Ejemplo subdirectorio Informe

      - **01_IGAC:** Informes generados directamente por el IGAC sobre las medidas y acciones sociales implementadas para el proceso catastral. Estos informes contienen información sobre las actividades sociales llevadas a cabo en el territorio, las interacciones con las comunidades, y los resultados de las acciones de sensibilización, participación y consulta

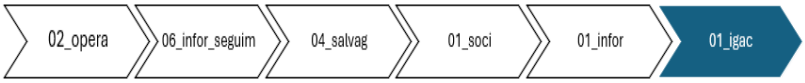

Diagrama 112. Ejemplo subdirectorio IGAC

- **02_Operador:** Informes generados por los operadores privados o terceros contratados para realizar el proceso catastral. Estos informes incluyen detalles sobre las actividades realizadas por los operadores en campo, el progreso del proyecto, las acciones correctivas implementadas y el cumplimiento de los plazos establecidos en los contratos.

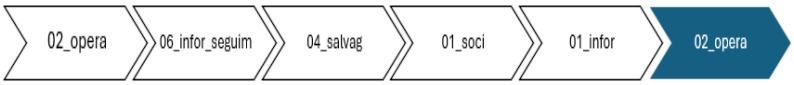

Diagrama 113. Ejemplo subdirectorio Operador

- **02_Mecanismo PQRSDF:** Documentos relacionados con los mecanismos establecidos para atender las peticiones, quejas, reclamos, sugerencias, denuncias y felicitación de la comunidad durante el proceso catastral y su seguimiento. Este archivo incluye los procedimientos, formularios, registros de recepción, respuesta a la PQRS, así como los informes de seguimiento sobre cómo se gestionan y resuelven las solicitudes de la comunidad.

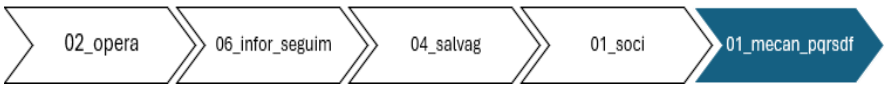

Diagrama 114. Ejemplo subdirectorio Mecanismos PQRSDF

- **02_Ambiental:** Documentación relacionada con las salvaguardas ambientales, respaldado por informes y estudios que evalúan el impacto ambiental de las actividades del levantamiento catastral, y las acciones implementadas para mitigar el daño al medio ambiente.

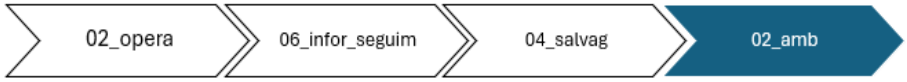

Diagrama 115. Ejemplo subdirectorio Ambiental

- **01_Informes:** Análisis y documentación del cumplimiento de las normativas ambientales, detallando las medidas adoptadas para evitar o mitigar impactos negativos en el medio ambiente, como la preservación de áreas protegidas, gestión de residuos generados en campo, entre otros.

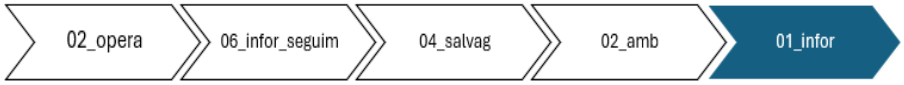

Diagrama 116. Ejemplo subdirectorio Informe

- **01_IGAC:** Informes generados directamente por el IGAC sobre las medidas y acciones ambientales implementadas para el proceso catastral.

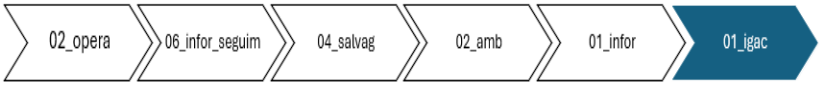

Diagrama 117. Ejemplo subdirectorio IGAC

- **02_Operador:** Informes generados por los operadores privados o terceros contratados para realizar el proceso catastral.

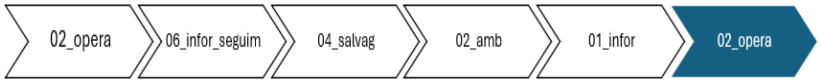

Diagrama 118. Ejemplo subdirectorio Operador

- **05_Seguimiento_saldos_conservación:** Registros relacionados con los saldos de conservación de la información catastral, que incluyan detalles sobre la calidad e integridad de los datos recolectados, con el fin de garantizar la confiabilidad de la información a lo largo del proceso de levantamiento catastral.

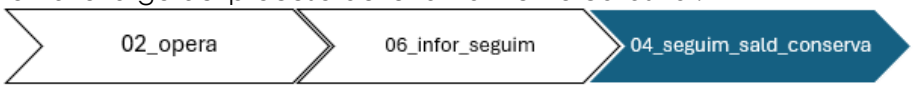

Diagrama 119. Ejemplo subdirectorio Seguimiento Saldos de conservación

- **07_Facturación:** Asegurar la correcta gestión y seguimiento de los pagos relacionados con el proceso catastral, incluyendo todos los documentos y registros necesarios para gestionar las facturas, los pagos a los proveedores y contratistas involucrados y cualquier otro gasto relacionado con este. Contiene facturas emitidas, recibos de pago, detalles de las transacciones financieras y los informes de estado de cuentas, que aseguren el cumplimiento de las obligaciones financieras.

Diagrama 120. Ejemplo subdirectorio Facturación

- **01_Primer_Pago:** Realizado tras la ejecución de actividades iniciales del levantamiento catastral, en recolección de datos o validación de información en terreno. Incluye facturas, recibos, informes de avance y cualquier otro documento que certifique que las actividades iniciales fueron completadas de acuerdo con los términos establecidos en el contrato.

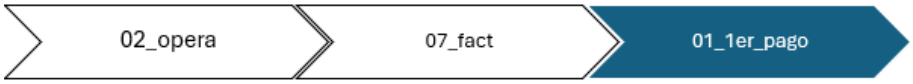

Diagrama 121. Ejemplo subdirectorio Primer Pago

  - **01_Soporte (Correo/informe/producto):** Documentación que certifique el avance de acuerdo con el cronograma previsto, incluyendo informes de las actividades preliminares realizadas en campo o el diagnostico de zonas a catastrar, con las respectivas comunicaciones formales como correos electrónicos, cartas o actas que respalden la entrega de la información catastral que se está desarrollando según lo planeado.

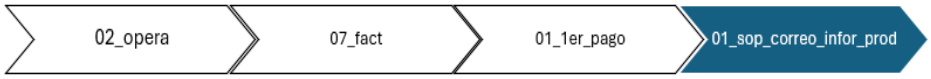

Diagrama 122. Ejemplo subdirectorio Soporte (Correo/informe/producto)

  - **02_Factura:** La factura debe estar vinculada a la entrega de los productos específicos que correspondan a cualquier actividad técnica y operativa

completada que justifique este primer desembolso, incluyendo una descripción detallada del desarrollo de la actividad y los costos requeridos.

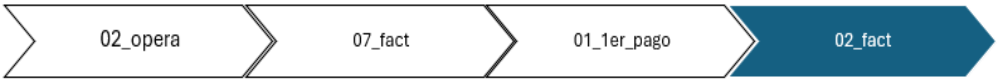

Diagrama 123. Ejemplo subdirectorio Factura

- **03_Oficio_Entrega:** Documentos oficiales que confirmen la entrega de los productos relacionados con el primer pago, con estos se certifica que los avances de recolección de datos catastrales han sido presentados formalmente, asegurando que se han cumplido los hitos establecidos en el cronograma.

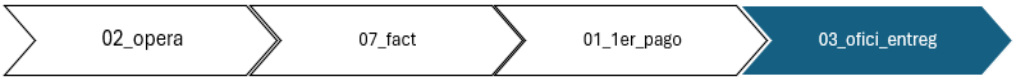

Diagrama 124. Ejemplo subdirectorio Oficio Entrega

- **04_Comprobante_Pago:** Comprobante de pago emitido, el cual puede ser un recibo bancario, una transferencia electrónica o documento oficial que respalde que el pago ha sido exitoso.

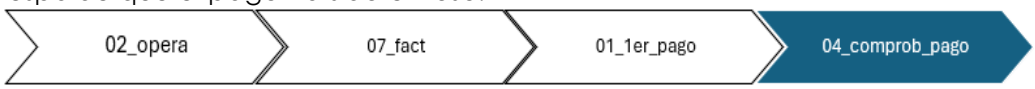

Diagrama 125. Ejemplo subdirectorio Comprobante Pago

- **02_Segundo_Pago:** Documentación necesaria para procesar el segundo pago, realizado tras un avance significativo en el levantamiento catastral, luego de la entrega de los primeros lotes de datos a procesar y validación de la información catastral correspondiente. Incluye informes, documentos de validación y cualquier otro material que respalde el cumplimiento de actividades de acuerdo con el cronograma del proyecto.

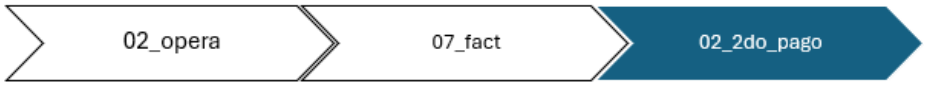

Diagrama 126. Ejemplo subdirectorio Segundo Pago

  - **01_Soporte (Correo/informe/producto):** Certifica el avance de acuerdo con el cronograma previsto, incluyendo informes de los avances del levantamiento en campo, como la recolección y validación de datos, y las comunicaciones formales que respaldan la entrega de los productos generados.

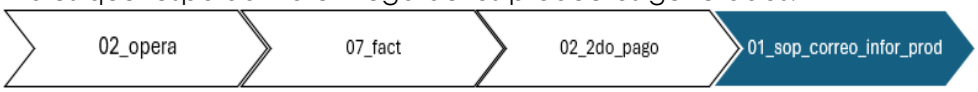

Diagrama 127. Ejemplo subdirectorio Soporte (Correo/informe/producto)

  - **02_Factura:** La factura debe estar vinculada a la entrega de los productos específicos relacionados con actividades técnicas y operativas completadas que justifiquen este segundo desembolso, incluyendo una descripción detallada de las actividades realizadas, el desarrollo de cada una de ellas y los costos asociados.

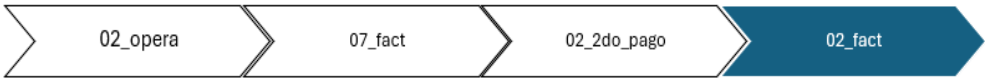

Diagrama 128. Ejemplo subdirectorio Factura

- **03_Oficio_Entrega:** Documentos oficiales que confirman la entrega de los productos relacionados con el segundo pago, con estos se certifica que los avances de recolección de datos catastrales han sido presentados formalmente, cumpliendo con los requisitos establecidos para este pago. El oficio de entrega actúa como prueba de que los entregables correspondientes a este avance han sido completados y entregados de acuerdo con el cronograma.

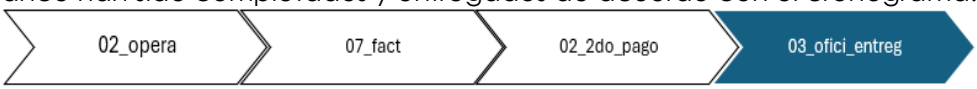

Diagrama 129. Ejemplo subdirectorio Oficio Entrega

- **04_Comprobante_Pago:** Comprobante de pago emitido, ya sea un recibo bancario, una transferencia electrónica o cualquier otro documento oficial que respalde que el pago ha sido exitoso.

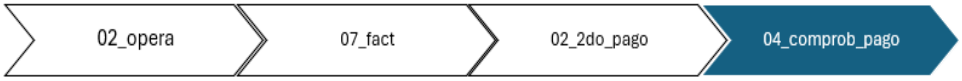

Diagrama 130. Ejemplo subdirectorio Comprobante Pago

- **03_Tercer_Pago:** Documentación requerida para procesar el último pago, el cual se efectúa una vez finalizado el proceso de levantamiento catastral. Esto incluye la consolidación definitiva de los datos catastrales, así como la entrega de los productos finales del levantamiento, asegurando que la información ha sido validada y entregada conforme a los requisitos establecidos.

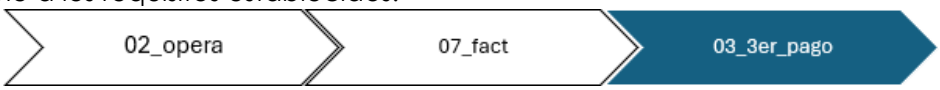

Diagrama 131. Ejemplo subdirectorio Tercer Pago

- **01_Soporte (Correo/informe/producto):** Documentación que certifica que el proceso de levantamiento catastral ha sido completado, soportado con informes finales, bases catastrales consolidadas, validación de la información catastral recolectada. Así mismo, debe existir evidencias de la revisión final de calidad y aprobación formal por la autoridad que tiene a cargo el proceso.

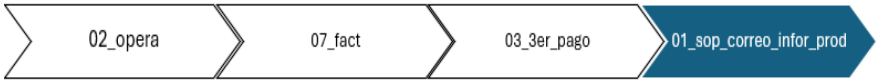

Diagrama 132. Ejemplo subdirectorio Soporte (Correo/informe/producto)

- **02_Factura:** La factura debe estar vinculada a la entrega final de todos los productos del proceso, consolidación de bases catastrales, y finalización de estudios territoriales. La factura debe detallar la finalización del desarrollo de la actividad y los costos requeridos.

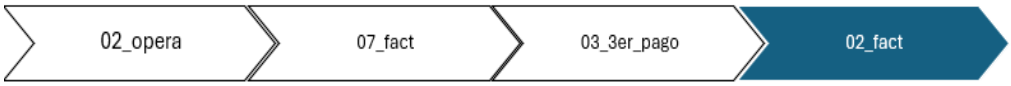

Diagrama 133. Ejemplo subdirectorio Factura

- **03_Oficio_Entrega:** Documento oficial que confirma la entrega de los productos finales, con esto se certifica que todo el trabajo ha sido completado y entregado de acuerdo con lo pactado.

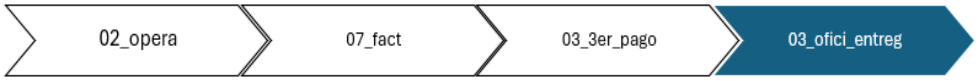

Diagrama 134. Ejemplo subdirectorio Oficio Entregado

- **04_Comprobante_Pago:** Comprobante de pago emitido, sea recibo bancario, transferencia electrónica o documento oficial que respalde que el pago ha sido exitoso tras la entrega final de los productos catastrales.

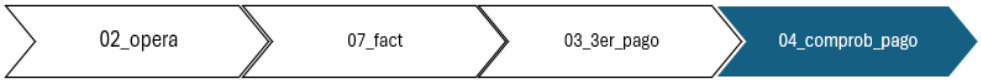

Diagrama 135. Ejemplo subdirectorio Comprobante Pago

De acuerdo con lo anterior, en la siguiente imagen se presenta las características de cada producto:

Dir_1	Dir_2	Dir_3	Dir_4	Dir_5	Dir_6	Contenido	Dir_7	Dir_8	Dir_9
			02_Operativos	01_Resolucion_Apertura	01_Resolución_de_Apertura	AAAAMMDD_publi_resol_apert.pdf AAAAMMDD_memo_resol_apert.pdf			
					02_Publicacion_Diario_Oficial	AAAAMMDD_publi_dia_ofic.pdf			
					03_Oficios_Comunicacion	AAAAMMDD_comuni_ini_proc.pdf			
				02_Componente_Social	01_Nivel_de_Interlocución_0 (*Acercamiento Regional*)	01_Informes	AAAAMMDD_infor_interloc_0.pdf		
						02_Registro_fotografico	AAAAMMDD_regis_fotog_medio_comuni_interloc_0.pdf AAAAMMDD_regis_fotog_und_interv_interloc_0.pdf		
						03_Listas_Asistencia	AAAAMMDD_list_asis_interloc_0.pdf		
						04_Difusión	AAAAMMDD_difus_interloc_0.pdf		
					02_Nivel_de_Interlocución_I (*Institucional/Comunitaria)*	01_Informes (*este incluye imágenes y mapas dibujados*)	AAAAMMDD_infor_interloc_1.pdf		
						02_Registro_fotografico	AAAAMMDD_regis_fotog_medio_comuni_interloc_1.pdf AAAAMMDD_regis_fotog_und_interv_interloc_1.pdf		
						03_Listas_Asistencia	AAAAMMDD_list_asis_interloc_1.pdf		
						04_Difusión	AAAAMMDD_difus_interloc_1.pdf		
					03_Nivel_de_Interlocución_II (**Líderes**)	01_Informes (**este incluye imágenes y mapas dibujados**)	AAAAMMDD_infor_interloc_2.pdf		
						02_Registro_fotografico	AAAAMMDD_regis_fotog_medio_comuni_interloc_2.pdf AAAAMMDD_regis_fotog_und_interv_interloc_2.pdf		
						03_Listas_Asistencia	AAAAMMDD_list_asis_interloc_2.pdf		
						04_Difusión	AAAAMMDD_difus_interloc_2.pdf		
					04_Nivel_de_Interlocución_III (*JAL y Comunidad*)	01_Informes	AAAAMMDD_infor_interloc_3.pdf		
						02_Registro_fotografico	AAAAMMDD_regis_fotog_medio_comuni_interloc_3.pdf AAAAMMDD_regis_fotog_und_interv_interloc_3.pdf		
						03_Listas_Asistencia	AAAAMMDD_list_asis_interloc_3.pdf		
						04_Difusión	AAAAMMDD_difus_interloc_3.pdf		
				03_Componente_Fisico_juridico	01_Base_Catastral_Aprobada	AAAAMMDD_base_catas_aprob_XXX.zip			
				04_Componente_Economico	AAAAMMDD_cronog_mitig_compo_econ_XXX.pdf AAAAMMDD_rta_solic_compo_econ_XXX.pdf AAAAMMDD_prop_ajus_fch_compo_econ_cto_XXX.pdf				
				05_CC_Seguimiento	aaaammdd	01_Hito	01_Rural	AAAAMMDD_infor_XXX_rur_hito_1.pdf	
							02_Urbano	AAAAMMDD_infor_XXX_urb_hito_1.pdf	
							03_Calidad	AAAAMMDD_repor_rev_calid_hito_1.pdf AAAAMMDD_matriz_hito_1.xlsx AAAAMMDD_matriz_XXX_ajus_hito_1.xlsx AAAAMMDD_pred_muest_hito_1.xlsx AAAAMMDD_fto_eval_calid_hito_1.xlsx	
						02_Hito	01_Rural	AAAAMMDD_infor_calid_rur_hito_2.pdf	
							02_Urbano	AAAAMMDD_infor_calid_urb_hito_2.pdf	
							03_Calidad	AAAAMMDD_repor_rev_calid_hito_2.pdf AAAAMMDD_matriz_hito_2.xlsx AAAAMMDD_matriz_XXX_ajus_hito_2.xlsx AAAAMMDD_pred_muest_hito_2.xlsx AAAAMMDD_fto_eval_calid_hito_2.xlsx	
				06_Informes_Seguimiento	01_Calculadora_Seguimiento	AAAAMMDD_calc_seguim_XXX.xlsx			
					02_Indicadores	AAAAMMDD_indicad_XXX.xlsx			
					03_Formatos_Seguimiento (Control de Calidad)	AAAAMMDD_cronog_XXX.xlsx AAAAMMDD_pred_XXX.xlsx AAAAMMDD_contr_detll_XXX.xlsx AAAAMMDD_tabir_XXX.xlsx			
					04_Salvaguardas	01_Social	01_informes	01_IGAC	AAAAMMDD_infor_salvag_soci_igac.pdf
								02_Operador	AAAAMMDD_infor_salvag_soci_XXX.pdf
							02_Mecanismo PQRSDD	AAAAMMDD_mecan_pqrsdf_soci.pdf	
						02_Ambiental	01_informes	01_IGAC	AAAAMMDD_infor_salvag_amb_igac.pdf
								02_Operador	AAAAMMDD_infor_salvag_amb_XXX.pdf
					05_Seguimiento_saldos_conservacion	AAAAMMDD_repor_infor_XXX.xlsx AAAAMMDD_ppt_proc_actualiz_catas_XXX.pptx AAAAMMDD_ppt_avan_arbitrium.pptx AAAAMMDD_seguim_arbitrium.pdf AAAAMMDD_cronog_XXX_arbitrium.xlsx AAAAMMDD_avan_XXX.xlsx			
				07_Facturacion	01_Primer_Pago	01_Soporte (correo/informe/producto)	AAAAMMDD_infor_prod.pdf AAAAMMDD_correo_prod.pdf AAAAMMDD_prod_final.pdf		
						02_Factura	AAAAMMDD_fact_elctrn_XXX.pdf AAAAMMDD_fact_aprob_XXX.pdf AAAAMMDD_rut_XX.pdf		
						03_Oficio Entrega	AAAAMMDD_entreg_ajus_XXX.pdf AAAAMMDD_infor_rta_vali_aprob_prod.pdf AAAAMMDD_rta_comuni.pdf		
						04_Comprobante_Pago	AAAAMMDD_comprob_pago_1.pdf		
					02_Segundo_Pago	01_Soporte (correo/informe/producto)	AAAAMMDD_infor_prod.pdf AAAAMMDD_correo_prod.pdf AAAAMMDD_prod_final.pdf		
						02_Factura	AAAAMMDD_fact_elctrn_XXX.pdf		
						03_Oficio Entrega	AAAAMMDD_entreg_ajus_XXX.pdf AAAAMMDD_fact_aprob_XXX.pdf		
						04_Comprobante_Pago	AAAAMMDD_comprob_pago_2.pdf		
					03_Tercer_Pago	01_Soporte (correo/informe/producto)	AAAAMMDD_infor_prod.pdf AAAAMMDD_correo_prod.pdf AAAAMMDD_prod_final.pdf		
						02_Factura	AAAAMMDD_fact_elctrn_XXX.pdf AAAAMMDD_fact_aprob_XXX.pdf		
						03_Oficio Entrega	AAAAMMDD_entreg_ajus_XXX.pdf		
						04_Comprobante_Pago	AAAAMMDD_comprob_pago_3.pdf		

Imagen 2. Etapa Operativa.

Para la Etapa Posoperativa se tiene:

- **01_Aprobación_Economica:** Análisis técnico y económico que sustenta la estructura y los valores catastrales definitivos para los predios en el municipio detallados en informes y evaluaciones que respaldan la aprobación económica final.

Diagrama 136. Ejemplo subdirectorio Aprobación Económica

  - **01_Informe_Tecnico_ZHG:** Documentos y estudios técnicos que detallan las áreas homogéneas geoeconómicas dentro del municipio a catastrar, definidas mediante el análisis de la estructura socioeconómica, el uso del suelo, y características geográficas que permiten identificar áreas con similitudes en capacidad económica y valor potencial.

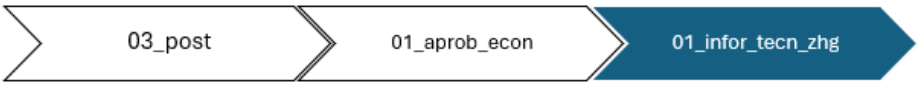

Diagrama 137. Ejemplo subdirectorio Informe Técnico ZHG

    - **01_Analisis_Sensibilidad:** Estudios que evalúan cómo diferentes variables como los cambios en el uso del suelo o las variaciones en el precio del mercado afectan las zonas homogéneas geoeconómicas.

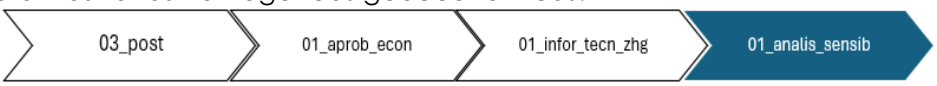

Diagrama 138. Ejemplo subdirectorio Análisis Sensibilidad

    - **02_Proyeccion_Avaluos:** Documentos basados en los resultados del análisis de zonas homogéneas, se generan las proyecciones que permitirán realizar los avalúos masivos de los terrenos y las construcciones en base a características homogéneas.

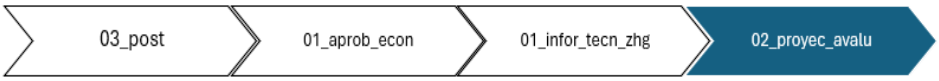

Diagrama 139. Ejemplo subdirectorio Proyección Avalúos

    - **03_Tablas_Terreno_Construccion:** Describe características específicas tanto de los terrenos como de las construcciones que se encuentran dentro de la zona homogénea geoeconómica, incluyendo detalles sobre el tipo de terreno, uso, ubicación geográfica, valor de mercado. Así mismo, las tablas relacionadas con las construcciones contienen información sobre el tipo de la edificación, el estado de conservación, antigüedad de las construcciones y todo lo que influye en el avalúo del predio.

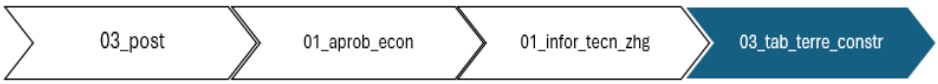

Diagrama 140. Ejemplo subdirectorio Tablas Terreno Construcción

  - **02_Acta_de_Comite:** Refleja las decisiones tomadas durante las reuniones de validación y revisión de los avances económicos del proyecto, esenciales para certificar que los recursos financieros asignados al proceso catastral han sido evaluados correctamente,

detallando la verificación de los costos involucrados, posibles variaciones en los gastos y revisión de informes financieros relacionados con el proceso de levantamiento catastral.

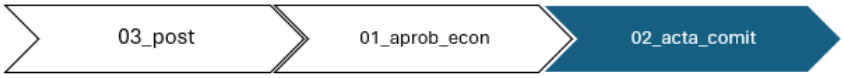

Diagrama 141. Ejemplo subdirectorio Acta de comité

- **03_Concepto_Favorable:** Validan la ejecución del presupuesto y aseguran que el levantamiento catastral se haya realizado conforme las normativas y dentro del presupuesto aprobado. Este informe técnico y administrativo certifica que los recursos han sido bien gestionados, sin desvíos financieros y siguiendo las normativas legales. Se incluyen informes de auditoría que respaldan que el proceso de levantamiento catastral haya sido ejecutado de acuerdo con los términos y condiciones acordados.

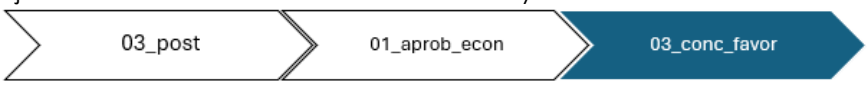

Diagrama 142. Ejemplo subdirectorio Concepto Favorable

- **04_Memoria_Tecnica_Estudio_Economico:** Resultados técnicos y económicos, justificando detalladamente las intervenciones realizadas, respaldando la toma de decisiones sobre la viabilidad y planificación del levantamiento catastral.

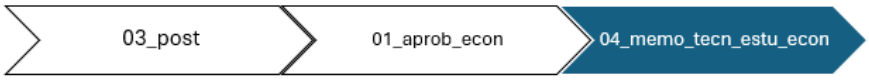

Diagrama 143. Ejemplo subdirectorio Memoria Técnica Estudio Económico

  - **01_Planos:** Gráficos fundamentales para consolidar la información obtenida en las fases anteriores, sean mapas, planos u otro tipo de representación visual del territorio catastral específicamente de las zonas urbanas y rurales que han sido catastradas con las áreas delimitadas, ubicación de predios e infraestructura relevante.

Diagrama 144. Ejemplo subdirectorio Plano

    - **01_Urbano:** Planos generados para las áreas urbanas, los cuales se centran en las características específicas de la urbanización, como división de predios, trazado de calles y carreteras, zonas de uso público redes de servicio, entre otros, que son esenciales para la planificación urbana.

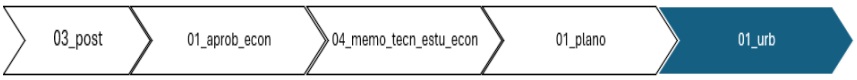

Diagrama 145. Ejemplo subdirectorio Urbano

    - **02_Rural:** Planos generados para las áreas rurales, que muestran la distribución de terrenos agrícolas, áreas forestales, cuerpos de agua y demás elementos territoriales de relevancia para el proceso catastral.



Diagrama 146. Ejemplo subdirectorio Rural

- **02_ZHF_ZHG (Terreno/construcción/predicación):** Las zonas homogéneas físicas y zonas homogéneas geoeconómicas son fundamentales para la clasificación de las áreas de acuerdo con sus características físicas y usos económicos. El plano de las ZHF deberá contener la elaboración y verificación de ZHF urbanas y/o rurales, dependiendo del área de intervención. Debe ser suministrado en medio digital, formato de entrega PDF con su respectivo archivo fuente (.gdb).

  El plano de ZHG deberá ser entregado de manera detallada con el procesamiento de la información que genere el cálculo de las ZHG conforme lo establece la metodología. Elaboración del estudio de ZHF y ZHG y determinación del valor unitario por tipo de construcción del IGAC.
  Dentro de esta carpeta se deben adjuntar además los documentos de relación de puntos fijados para investigación económica, investigación directa e indirecta del mercado inmobiliario. Estimación precio unitario investigación directa e indirecta, cálculo de ZHG, informe de verificación del estudio de ZHF, valores unitarios de construcción, cálculo de regresión, tamaño de la muestra para puntos, protocolo de validación del estudio de zonas homogéneas, y memoria de avalúo puntos de Investigación económica para determinación de valores unitarios de terreno y construcción en formato (.xlsx). Deberá ser suministrado en medio digital, formato de entrega PDF con su respectivo archivo fuente (.gdb).

Diagrama 147. Ejemplo subdirectorio ZHF y ZHG

  - **01_2023:** Documentos y estudios correspondientes a ZHF y ZHG generados en el año 2023, que abordan la clasificación y análisis de las zonas catastrales.

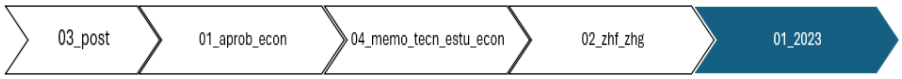

Diagrama 148. Ejemplo subdirectorio 2023

  - **02_2024:** Documentos y estudios correspondientes a ZHF y ZHG generados en el año 2024, que abordaron la clasificación y análisis de las zonas catastrales, pero con los ajustes y nuevas mediciones que se hayan realizado durante este año.



Diagrama 149. Ejemplo subdirectorio 2024

- **03_Formatos:** Formatos y plantillas utilizadas para la recolección de datos en campo, y su posterior análisis.

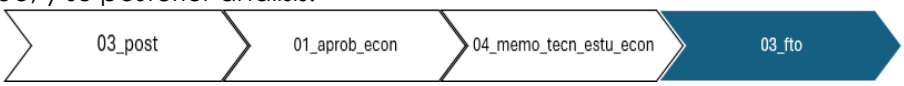

Diagrama 150. Ejemplo subdirectorio Formatos

- **01_Urbano:** Formatos específicos utilizados para la recolección de datos en zonas urbanas, con información sobre la delimitación de predios, características de edificaciones, uso del suelo, etc.

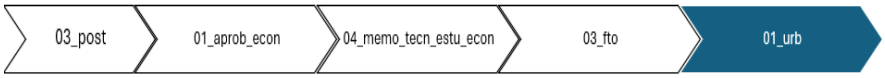

Diagrama 151. Ejemplo subdirectorio Urbano

  - **01_2023:** Actualizaciones y ajustes realizados en los datos catastrales durante el periodo 2023.

Diagrama 152. Ejemplo subdirectorio 2023

  - **02_2024:** Actualizaciones y ajustes realizados en los datos catastrales durante el periodo 2024.

Diagrama 153. Ejemplo subdirectorio 2024

- **02_Rural:** Formatos específicos utilizados para la recolección de datos en zonas rurales, que tienen en cuenta aspectos como la clasificación de tierras agrícolas, propiedades rurales y características de la infraestructura en áreas no urbanizadas.

Diagrama 154. Ejemplo subdirectorio Rural

  - **01_2023:** Actualizaciones y ajustes realizados en los datos catastrales durante el periodo 2023.

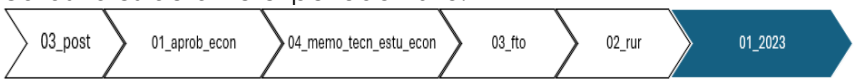

Diagrama 155. Ejemplo subdirectorio 2023

  - **02_2024:** Actualizaciones y ajustes realizados en los datos catastrales durante el periodo 2024.

Diagrama 156. Ejemplo subdirectorio 2024

- **03_Urbano_rural:** Formatos mixtos utilizados en zonas donde se combinan áreas urbanas y rurales, para municipios donde los límites entre zonas urbanas y rurales no están claramente definidos y en donde el catastro abarca terrenos tanto urbanos como rurales.

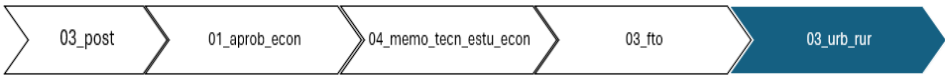

Diagrama 157. Ejemplo subdirectorio Urbano y Rural

- **01_2023:** Actualizaciones y ajustes realizados en las áreas mixtas durante 2023, abarcando tanto características urbanísticas como rurales, e integrando los datos catastrales de estos dos tipos de terrenos.

Diagrama 158. Ejemplo subdirectorio 2023

- **02_2024:** Actualizaciones y ajustes realizados en las áreas mixtas durante 2024, abarcando tanto características urbanísticas como rurales, e integrando los datos catastrales de estos dos tipos de terrenos.

Diagrama 159. Ejemplo subdirectorio 2024

- **04_Memoria:** Documentos que explican los enfoques metodológicos, toma de decisiones durante la fase de recolección y procesamiento de los datos catastrales.

Diagrama 160. Ejemplo subdirectorio Memoria

  - **01_Urbano:** Informes que incluyen un análisis de los procesos realizados en las áreas urbanas, delimitación de áreas, recolección sobre edificaciones y análisis de la distribución del uso del suelo.

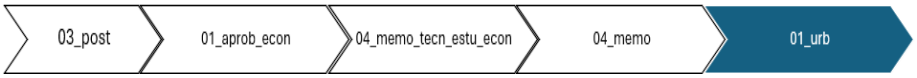

Diagrama 161. Ejemplo subdirectorio Urbano

  - **02_Rural:** Informes que incluyen un análisis de los procesos realizados en las áreas rurales, clasificación y uso de la tierra y resultados de recolección de datos sobre terrenos agrícolas, forestales, entre otros.

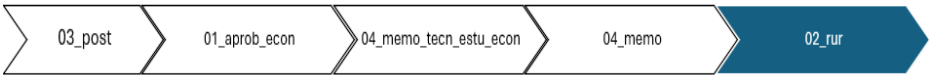

Diagrama 162. Ejemplo subdirectorio Rural

- **05_Comunicacion_Adopción_Porcentaje_Avaluo_Catastral:** Comunicaciones y documentos emitidos para informar a los actores sociales, autoridades locales, y entidades responsables sobre los ajustes realizados en el porcentaje de los avalúos catastrales, buscando aclarar a la comunidad cómo se llegó a la nueva valoración de sus propiedades y cumplimiento de los requisitos legales y normativos.

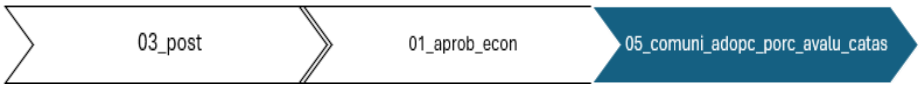

Diagrama 163. Ejemplo subdirectorio Comunicación adopción porcentaje avalúo catastral

- **06_Resolución_Aprobación:** Respalda la aprobación de los procedimientos económicos y técnicos de las decisiones tomadas. El análisis contiene gráficos comparativos y reportes con referencias al marco normativo del IGAC incluyendo minutas de reuniones y oficios internos durante el proceso de aprobación.

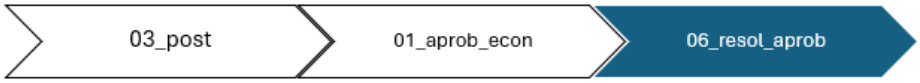

Diagrama 164. Ejemplo subdirectorio Resolución aprobación

- **01_Resolucion:** Resultado del análisis de los costos asociados al proceso, verificando cifras y que se cumpla con los objetivos establecidos con el fin de garantizar la trazabilidad y respaldo para cualquier auditoría o revisión.

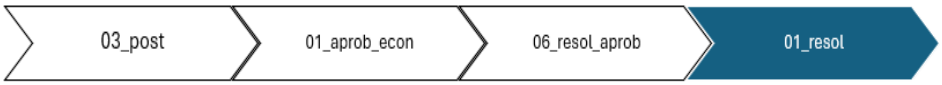

Diagrama 165. Ejemplo subdirectorio Resolución

- **02_Publicacion_Diario_Oficial:** Divulgación normativa de las resoluciones, asegurando transparencia hacia la ciudadanía y confirma la validez de las decisiones adoptadas como lo exige la normativa catastral y administrativa del IGAC, consolidando así el carácter público del proceso catastral.

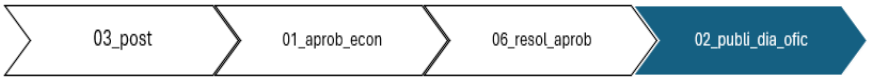

Diagrama 166. Ejemplo subdirectorio Publicación Diario Oficial

- **03_Oficios_Comunicacion:** Comunicación oficial relacionada con la aprobación económica, enviados a las partes interesadas, como entidades gubernamentales, contratistas o beneficiarios del levantamiento catastral. Estos documentos son evidencia de la difusión de las resoluciones aprobadas.

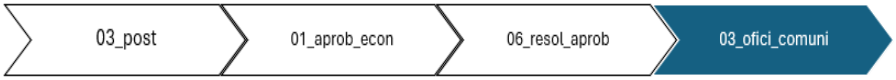

Diagrama 167. Ejemplo subdirectorio Oficios Comunicación

- **02_Componente_Social:** Involucrar a los actores locales, buscando que se comprenda el proceso, validando los resultados y minimizando conflictos. Se expone la información predial recolectada durante las etapas previas permitiendo a los propietarios y poseedores corroborar, y en caso de ser necesario, solicitar corrección a los datos recolectados.

Diagrama 168. Ejemplo subdirectorio Oficios Comunicación

- **01_Nivel_Interlocución_IV (Exposición de Resultados/Cierre Operación):** Involucrar a las comunidades y actores locales, para la entrega de información consolidada sobre la actualización catastral de predios, presentación de mapas, estadísticas, y reportes en donde se refleje la realidad predial. De esta manera, se formaliza la finalización del proceso, asegurando que todas las actividades técnicas y sociales estén debidamente documentadas y entregadas. Debe contener las actas de socialización de cierre de Operación Catastral Multipropósito, registros de asistencia, registros fotográficos, sonoros y/o audiovisuales correspondientes al evento, formatos de encuesta de satisfacción del evento diligenciadas, informe realización socialización de cierre de la operación. Deberán ser suministrados en formato PDF, JPG, MP4, entre otros.

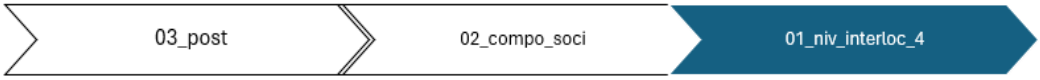

Diagrama 169. Ejemplo subdirectorio Nivel de Interlocución IV

- **01_Informes:** Documentos técnicos generados al cierre del proceso catastral, incluyendo estadísticas del alcance en términos de cobertura, precisión y resultados obtenidos, como también orientados a presentar un balance completo del impacto en la comunidad.

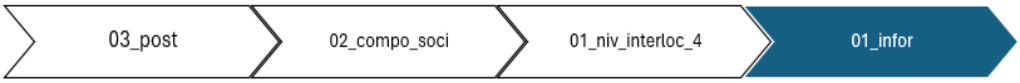

Diagrama 170. Ejemplo subdirectorio Informes

- **02_Registro_Fotografico:** Evidencias fotográficas que sustentan los resultados presentados de actividades realizadas durante el proceso catastral, incluyendo reuniones con la comunidad, visitas a predios, y validaciones técnicas en campo. Cada fotografía está asociada a un registro que especifica el lugar, la fecha y la actividad realizada para corroborar la información presentada en los informes ante posibles controversias.

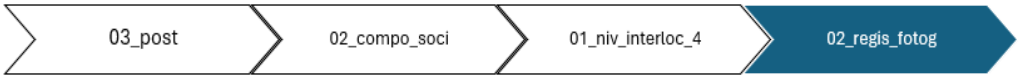

Diagrama 171. Ejemplo subdirectorio Registro Fotográfico

- **03_Listas_Asistencia:** Listas de asistencia de los eventos relacionados con la exposición de resultados, la participación de los actores, lideres comunitarios, propietarios de predios, representantes institucionales, con datos como nombres, cargos, firmas, y observaciones específicas.

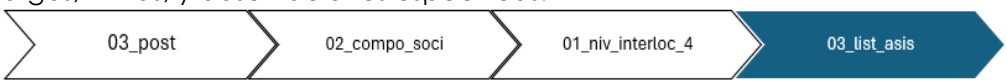

Diagrama 172. Ejemplo subdirectorio Lista Asistencia

- **04_Difusión:** Materiales como folletos, carteles, volantes, correos, publicaciones en redes sociales, páginas web o comunicados de prensa emitidos por el IGAC o autoridades locales que se distribuyen de los resultados del proceso catastral, asegurando que estos sean conocidos, aceptados y validos por los involucrados.

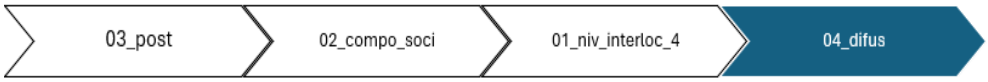

Diagrama 173. Ejemplo subdirectorio Difusión

- **03_Pre-Cierre:** Fase de verificación y ajustes finales antes de cerrar el proceso, haciendo control exhaustivo sobre los datos recolectados, asegurar que todos los errores hayan sido corregidos y validar que toda la información esté lista para ser consolidada y cerrada oficialmente.

Diagrama 174. Ejemplo subdirectorio Pre-cierre

  - **01_Evidencias_Atención_Saldos:** Solicitudes de aclaración, corrección de datos o inclusión de nuevos elementos en la base catastral. Se registran todas las evidencias relacionadas con la gestión de estos saldos, como informes de revisión, los registros de comunicación con los propietarios o entidades locales, y las respuestas a las objeciones que hayan surgido durante la fase operativa del levantamiento catastral.

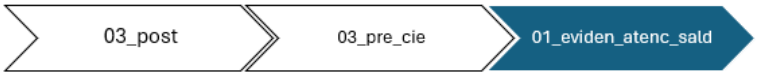

Diagrama 175. Ejemplo subdirectorio Evidencias atención saldos

  - **02_Reportes_CICA_finales:** Consolidan la información sobre los predios, mediciones realizadas, límites territoriales y características específicas de cada propiedad, sin embargo, no solo tienen valor técnico, sino que también son utilizados para la socialización y validación con las comunidades y para la toma de decisiones.

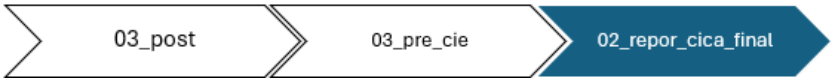

Diagrama 176. Ejemplo subdirectorio Reportes CICA finales

  - **03_Base_Renumeración:** Asigna un identificador único y oficial a cada predio, lo que facilita su localización y gestión en el sistema catastral, asegurando que todos los predios estén correctamente registrados y etiquetados con la información adecuada, y que no haya duplicados o errores en el sistema. Se revisa y ajusta esta base para corregir posibles errores o inconsistencias antes de la validación final.

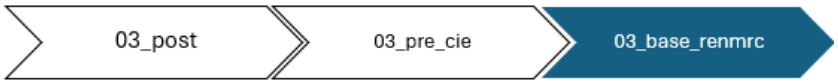

Diagrama 177. Ejemplo subdirectorio Base Renumeración

  - **04_Tabla_PH:** Gestión de la información relacionada con los predios en régimen de propiedad horizontal, como apartamentos, oficinas, oficinas dentro de un edificio o complejo inmobiliario, debe ser registrado y reflejar aspectos individuales (área, ubicación, número de registro) como aspectos comunes (zonas comunes del edificio), con información técnica de estos predios, y tener la correcta identificación y registro de propiedades dentro de este régimen.

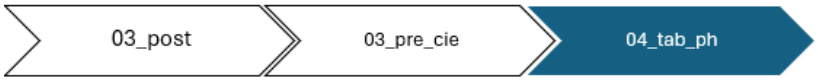

Diagrama 178. Ejemplo subdirectorio Tabla PH

- **05_Preliquidacion:** Cálculos y análisis preliminares sobre los valores catastrales que se utilizarán para determinar impuestos prediales, contribuciones y otros aspectos financieros con relación a la propiedad, revisando la base catastral para asegurarse de que todos los valores sean correctos, basados en la ubicación, uso del suelo, área, etc., detectando posibles errores de valoración antes de que se realicen las liquidaciones finales.

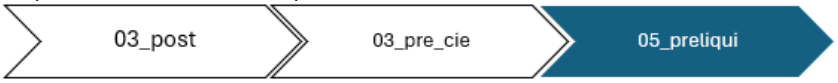

Diagrama 179. Ejemplo subdirectorio Preliquidación

- **04_Resolución_Inscripción:** Oficializar y comunicar los cambios o actualizaciones catastrales a los propietarios, que da cierre administrativo y legal al proceso, formalizando los cambios en el registro catastral a través de resoluciones y posterior publicación.

Diagrama 180. Ejemplo subdirectorio Resolución Inscripción

  - **01_Resolución:** Resoluciones oficiales que formalizan la inscripción de los predios intervenidos. Contienen la descripción de los cambios registrados en cada propiedad, como modificaciones en linderos, áreas, avalúos o cambios de uso del suelo, todo sustentado en los datos recolectados durante el levantamiento catastral, incluyendo fundamentos legales que respaldan la decisión y garantiza su validez jurídica.

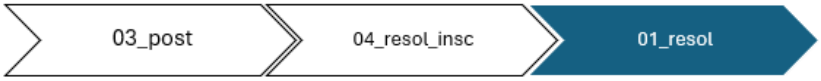

Diagrama 181. Ejemplo subdirectorio Resolución

  - **02_Publicación_Diario_Oficial:** Copias digitalizadas de publicaciones, como certificaciones o resoluciones emitidas en el diario oficial u otros medios públicos exigidos por la normativa vigente, son fundamentales para asegurar la transparencia. Esto garantiza que las modificaciones sean de conocimiento público, lo cual resulta relevante para los propietarios de los predios.

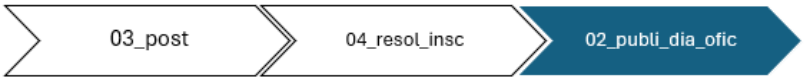

Diagrama 182. Ejemplo subdirectorio Publicación Diario Oficial

  - **03_Oficios_Comunicación_Resolución:** Los oficios detallan de manera específica los cambios realizados en los predios, proporcionando información clara y precisa sobre las modificaciones catastrales, como ajustes en linderos, áreas, avalúos u otra característica registrada. Además, incluyen las instrucciones necesarias para que los propietarios y partes interesadas puedan presentar observaciones, solicitudes de aclaración o apelaciones dentro de los plazos establecidos por la normativa vigente. Para garantizar la evidencia o trazabilidad de notificación, se adjuntan acuses de recibo firmados o confirmaciones electrónicas de la recepción de estos documentos, asegurando que la comunicación fue entregada de manera efectiva y dentro de los tiempos estipulados.

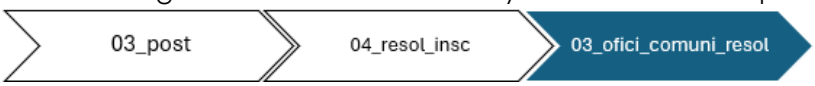

Diagrama 183. Ejemplo subdirectorio Oficios comunicación resolución

- **05_Productos_catastrales:** Resultados finales del proceso de actualización catastral. Estos productos reflejan el esfuerzo por garantizar que toda la información generada sea clara, consistente y cumpla con las normas legales. Así mismo, aseguran la trazabilidad del proceso, brindando confianza a los propietarios y facilitando acceso a los datos catastrales actualizados.

Diagrama 184. Ejemplo subdirectorio Productos Catastrales

  - **01_Listado_Predios_Actualizados:** Listado consolidado de los predios que han sido objeto de actualización catastral durante el proceso, agregando identificadores únicos como el código predial, información sobre el propietario o poseedor, área actualizada y modificaciones realizadas a cada predio.

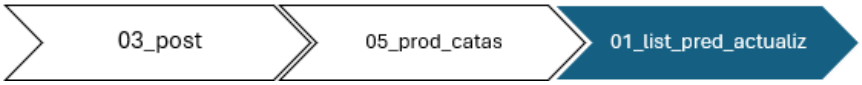

Diagrama 185. Ejemplo subdirectorio Listado Predios Actualizados

  - **02_Memoria_Tecnica_Actualización:** Describe las metodologías, herramientas y técnicas durante el levantamiento y procesamiento de datos como los softwares empleados para la edición y verificación de datos. Explica las justificaciones técnicas de las decisiones tomadas, como ajustes de linderos o correcciones en la base cartográfica.

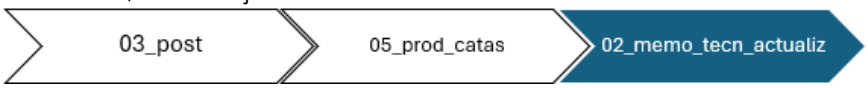

Diagrama 186. Ejemplo subdirectorio Memoria Técnica Actualización

  - **03_R1 y R2:** Reúne los formatos de registro R1 y R2 que son esenciales para consolidar la información catastral en términos de la base física (R1) y económica (R2). En el formato R1, se documentan características físicas de los predios, como ubicación, área, linderos y construcciones asociadas. En el formato R2, se integran los aspectos económicos, incluyendo el avalúo catastral, las tarifas aplicadas y cualquier ajuste tributario derivado del proceso de actualización.

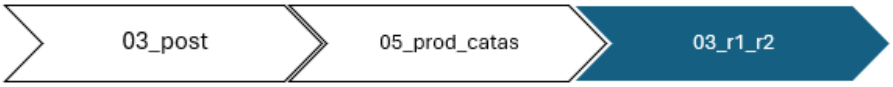

Diagrama 187. Ejemplo subdirectorio R1 y R2

  - **04_GDB:** Base de datos geoespacial, que contiene las capas geográficas que representan los predios, zonas homogéneas físicas y geoeconómicas, vías de acceso, puntos de control, etc. Cada capa incluye atributos descriptivos asociados que permiten la consulta y análisis mediante herramientas geoespaciales.

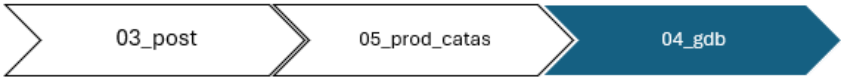

Diagrama 188. Ejemplo subdirectorio GDB

  - **05_XTF:** Alberga los archivos generados para la transferencia de datos catastrales entre sistemas interoperables, esto para el intercambio de información catastral y geoespacial, asegurando que los datos cumplan con los estándares de validez y compatibilidad. Se tienen datos geométricos y descriptivos de los predios, lo que permite su correcta integración para la entrega de productos catastrales.

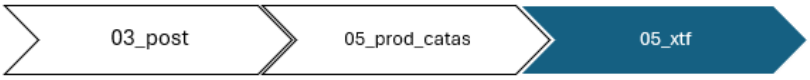

Diagrama 189. Ejemplo subdirectorio XTF

- **06_Acta_Entrega_Base_Catastral:** Formaliza la transferencia de la base de datos catastral actualizada al cliente o entidad receptora, generalmente alcaldía, gobernación o autoridad territorial. En el acta se especifica los datos entregados, formatos utilizados, incluyendo información como los registros gráficos (cartografía), registros alfanuméricos (datos descriptivos de los predios) y componentes normativos (uso del suelo y zonificación).

Diagrama 190. Ejemplo subdirectorio Acta Entrega Base Catastral

- **07_Acta_de_Entrega_Productos_Catastrales:** Transferencia formal de los productos generados durante el proceso, enfocado en los resultados finales, que incluye informes técnicos, listados actualizados en predios, resoluciones de inscripción catastral y bases de datos geoespaciales. Se especifica el estado de los productos al momento de la entrega, revisando si hay versiones preliminares, finales o en proceso de revisión.

Diagrama 191. Ejemplo subdirectorio Acta Entrega Productos Catastrales

De acuerdo con lo anterior, en la siguiente imagen se presenta las características de cada producto:

Dir_4	Dir_5	Dir_6	Contenido	Dir_7	Dir_8	Dir_9
03_Posoperativo	01_Aprobación_Economica	01_Informe_Tecnico_ZHG	01_Analisis_Sensibilidad	AAAAMMDD_preliqui_XXX.xlsx		
			02_Proyeccion_Avaluos	AAAAMMDD_preliqui_XXX.xlsx		
			03_Tablas_Terreno_Construccion	AAAAMMDD_tabl_terre_constr_XXX.xlsx		
		02_Acta_de_Comite	AAAAMMDD_acta_comit_avalu.pdf			
		03_Concepto_Favorable	AAAAMMDD_conc_favor_resol_XX.pdf			
		04_Memoria_Tecnica_Estudio_Economico	01_Planos	01_urb	AAAAMMDD_plano_XXX_urb.pdf	
				02_rur	AAAAMMDD_plano_XXX_rur.pdf	
			02_ZHF_ZHG (Terreno/construccion/prediacion)	2023	AAAAMMDD_bd_XX_zhf_zhg.zip	
				2024	AAAAMMDD_bd_XX_zhf_zhg.zip	
			03_Formatos	01_urb	2023 (Vigencia)	AAAAMMDD_estim_precio_unt_invest_urb.pdf AAAAMMDD_invest_merc_inmob_urb.pdf AAAAMMDD_zhf_urb.pdf AAAAMMDD_valo_zhg_urb.pdf AAAAMMDD_calc_zhg_urb.pdf AAAAMMDD_rela_pto_fija_invest_econ_urb.pdf
					2024 (Vigencia)	AAAAMMDD_estim_precio_unt_invest_urb.pdf AAAAMMDD_invest_merc_inmob_urb.pdf AAAAMMDD_zhf_urb.pdf AAAAMMDD_valo_zhg_urb.pdf AAAAMMDD_calc_zhg_urb.pdf AAAAMMDD_rela_pto_fija_invest_econ_urb.pdf
				02_rur	2023 (Vigencia)	AAAAMMDD_estim_precio_unt_invest_rur.pdf AAAAMMDD_invest_merc_inmob_rur.pdf AAAAMMDD_zhf_rur.pdf AAAAMMDD_valo_zhg_rur.pdf AAAAMMDD_calc_zhg_rur.pdf AAAAMMDD_rela_pto_fija_invest_econ_rur.pdf
					2024 (Vigencia)	AAAAMMDD_estim_precio_unt_invest_rur.pdf AAAAMMDD_invest_merc_inmob_rur.pdf AAAAMMDD_zhf_rur.pdf AAAAMMDD_valo_zhg_rur.pdf AAAAMMDD_calc_zhg_rur.pdf AAAAMMDD_rela_pto_fija_invest_econ_rur.pdf
				03_urb_rur	2023 (Vigencia)	AAAAMMDD_estim_precio_unt_invest_urb_rur.pdf AAAAMMDD_invest_merc_inmob_urb_rur.pdf AAAAMMDD_zhf_urb_rur.pdf AAAAMMDD_valo_zhg_urb_rur.pdf AAAAMMDD_calc_zhg_urb_rur.pdf AAAAMMDD_rela_pto_fija_invest_econ_urb_rur.pdf
					2024 (Vigencia)	AAAAMMDD_estim_precio_unt_invest_urb_rur.pdf AAAAMMDD_invest_merc_inmob_urb_rur.pdf AAAAMMDD_zhf_urb_rur.pdf AAAAMMDD_valo_zhg_urb_rur.pdf AAAAMMDD_calc_zhg_urb_rur.pdf AAAAMMDD_rela_pto_fija_invest_econ_urb_rur.pdf
			04_Memoria	01_urb	AAAAMMDD_memo_tecn_estu_econ_urb.pdf	
				02_rur	AAAAMMDD_memo_tecn_estu_econ_rur.pdf	
		05_Comunicación_Adopción_Porcentaje_Avaluo_Catastral	AAAAMMDD_solic_ini_tram_admin.pdf			
			AAAAMMDD_preliqui_XXX.xlsx			
		06_Resolución_Aprobación	01_Resolución	AAAAMMDD_resol_aprob.pdf		
			02_Publicacion_Diario_Oficial	AAAAMMDD_publi_dia_ofic.pdf		
			03_Oficios_Comunicacion	AAAAMMDD_preliqui_XXX.xlsx		
				AAAAMMDD_solic_ini_tram_admin_XXX.pdf		
	02_Componente_Social	01_Nivel_Interlocución_IV (*Exposicion de Resultados/Cierre Operación*)	01_Informes	AAAAMMDD_infor_interloc_4.pdf		
			02_Registro_fotografico	AAAAMMDD_regis_fotog_medio_comuni_interloc_4.pdf		
				AAAAMMDD_regis_fotog_und_interv_interloc_4.pdf		
			03_Listas_Asistencia	AAAAMMDD_list_asis_interloc_4.pdf		
			04_Difusión	AAAAMMDD_difus_interloc_4.pdf		
	03_Pre-Cierre	01_Evidencias_Atención_Saldos	AAAAMMDD_pred_conserva_catas.xlsx			
		02_Reportes_CICA_Finales	AAAAMMDD_pred_XX.xlsx			
		03_Base_Renumeración	AAAAMMDD_XXX_renum.xlsx			
		04_Tabla_PH	AAAAMMDD_tab_terre_constr_XXX.xlsx			
		05_Preliquidación	AAAAMMDD_avalu_x_pred.xlsx			
			AAAAMMDD_consul_comi.xlsx			
			AAAAMMDD_dife_area_mayor.xlsx			
			AAAAMMDD_dife_area_menor.xlsx			
			AAAAMMDD_preliqui_cica_snc_XXX.xlsx			
			AAAAMMDD_estd_x_zon_geoe.xlsx			
			AAAAMMDD_pred_no_liqui.xlsx			
	04_Resolución_Inscripcion	01_Resolución	AAAAMMDD_resol_insc_XXX.pdf			
		02_Publicacion_Diario_Oficial	AAAAMMDD_publi_dia_ofic.pdf			
		03_Oficios_Comunicacion_Resolucion	AAAAMMDD_resol_aprob_XXX.pdf			
			AAAAMMDD_resol_insc_XXX.pdf			
			AAAAMMDD_entreg_base_catas_XX.pdf			
	05_Productos_catastrales	01_Listado_Predios_Actualizados	AAAAMMDD_list_pred_actualiz.xlsx			
		02_Memoria_Tecnica_Actualizacion	AAAAMMDD_memo_tecn_actualiz.pdf			
		03_R1 y R2	AAAAMMDD_infor_r1.xlsx			
			AAAAMMDD_infor_r2.xlsx			
		04_GDB	AAAAMMDD_entreg_bd_geo_catas.pdf			
			AAAAMMDD_gdb_XX.zip			
		05_XTF	AAAAMMDD_XX.xtf			
	06_Acta_Entrega_Base_Catastral	AAAAMMDD_acta_entreg_base_catas.pdf				
	07_Acta_de_Entrega_Productos_Catrastrales	AAAAMMDD_acta_entreg_prod_catas.pdf				

Imagen 3. Etapa Postoperativa.

Para la Etapa Transversal se tiene:

- **1_Correspondencia:** Preserva toda la correspondencia oficial generada y recibida a lo largo del proyecto, asegurando un historial claro de las interacciones entre los diferentes actores.

Diagrama 192. Ejemplo subdirectorio Correspondencia

  - **01_Correspondencia_Enviada:** Correspondencia oficial emitida por el equipo catastral del IGAC, como cartas, memorandos, y notificaciones enviadas a entidades territoriales, contratistas, o comunidad involucrada. Estos documentos incluyen confirmaciones de reuniones, solicitud de permisos para ingreso a predios, requerimientos de información y notificaciones de los avances o resultados. Cada archivo debe estar debidamente fechado, identificado por asunto, y categorizado para facilitar la consulta, como también tener copias de correos electrónicos importantes respaldados por una firma digital.

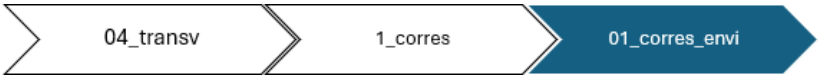

Diagrama 193. Ejemplo subdirectorio Correspondencia enviada

  - **02_Correspondencia_Recibida:** Comunicaciones de autoridades locales, propietarios de predios, o contratistas, como respuestas a solicitudes, autorizaciones para acceso a terrenos y observaciones sobre los productos entregados. Cada documento tiene un registro cronológico y una breve descripción de su contenido.

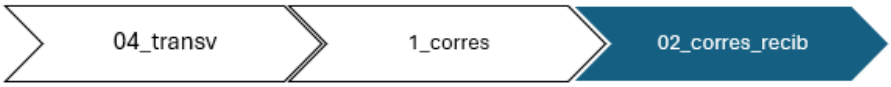

Diagrama 194. Ejemplo subdirectorio Correspondencia recibida

- **2_Asistencias:** Registros de participación en actividades expuestas en el proceso, como capacitaciones y reuniones, cuenten con evidencia documentada de su desarrollo y participación.

Diagrama 195. Ejemplo subdirectorio Asistencia

  - **01_Capacitaciones:** Listas de asistencia firmadas por los participantes, temarios de las capacitaciones, materiales didácticos entregados, y evaluaciones realizadas al final de cada sesión.

Diagrama 196. Ejemplo subdirectorio Capacitaciones

  - **02_Reuniones:** Documenta las reuniones internas y externas con autoridades territoriales, comunidades y contratistas, en las que discuten temas como avance del proyecto, ajustes técnicos o resolución de conflictos.

Diagrama 197. Ejemplo subdirectorio Reuniones

- **3_Presentaciones:** Compila los materiales visuales y gráficos utilizados para comunicar información con autoridades locales y con la comunidad, con presentaciones en PowerPoint, gráficos estadísticos, y mapas temáticos diseñados para explicar los avances y resultados del proyecto.

Diagrama 198. Ejemplo subdirectorio Presentaciones

- **4_HSEQ:** Estándares de salud, seguridad, medio ambiente y calidad, como protocolos de seguridad para el personal en campo, planes de manejo ambiental para minimizar el impacto del levantamiento catastral, y reportes de cumplimiento con normas de calidad. Se tienen registros de inspecciones de seguridad, reportes de incidentes y acciones correctivas implementadas.

Diagrama 199. Ejemplo subdirectorio HSEQ

De acuerdo con lo anterior, en la siguiente imagen se presenta las características de cada producto:

TE	>	Dir_1	Dir_2	Dir_3	Dir_4	Dir_5	Dir_6	Contenido
					04_Transversal	1_Correspondencia	01_Correspondencia_Enviada	AAAAMMDD_rta_solic_XXX_cronog.pdf AAAAMMDD_rta_requerim_XXX.pdf AAAAMMDD_fto_eval_calid_extrm.xlsx AAAAMMDD_devol_entreg_prod_XXX.pdf
							02_Correspondencia_Recibida	AAAAMMDD_solic_prorr_cto_XX_mpio_XXX.pdf AAAAMMDD_cronog_trab_prop_mitig_compo_econ_XXX.pdf AAAAMMDD_correo_entreg_ajus_etp_XX.pdf AAAAMMDD_requerim_XXX.pdf AAAAMMDD_rta_snc_mpio_XXX.pdf
						2_Asistencias	01_Capacitaciones	AAAAMMDD_capacit_contr_calid_camp_dt_XXX.pdf AAAAMMDD_socializa_contr_calid_hito_XX.pdf AAAAMMDD_capacit_fto_eval_calid_XXX.xlsx AAAAMMDD_pto_invest_arbitrium.pdf
							02_Reuniones	AAAAMMDD_regis_asis_XXX.pdf AAAAMMDD_acta_reu_XXX.pdf AAAAMMDD_seguim_sema_XXX.pdf
						3_Presentaciones	AAAAMMDD_comit_seguim_actualiz_catas_XXX.pptx	
							AAAAMMDD_proc_actualiz_catas_XXX.pptx	
						4_HSEQ	AAAAMMDD_infor_hseq.pdf	

Imagen 4. Transversal.